Załącznik do uchwały Nr 850/2024
Zarządu PKP Polskie Linie Kolejowe S.A.
z dnia 10 września 2024 r.

PKP POLSKIE LINIE KOLEJOWE S.A.

Instrukcja o sporządzaniu i aktualizacji planów schematycznych Ig-10 [D-27]

Warszawa, 2024

Właściciel: PKP Polskie Linie Kolejowe S.A.
Wydawca: PKP Polskie Linie Kolejowe S.A. Centrala
Biuro Nieruchomości, Geodezji i Geoinformacji
ul. Targowa 74, 03-734 Warszawa
Tel.+48 22 473 20 68
www.plk-sa.pl, e-mail: igk@plk-sa.pl

Wszelkie prawa zastrzeżone.
Modyfikacja, wprowadzanie do obrotu, publikacja, kopiowanie i dystrybucja w celach komercyjnych, całości lub części przepisu, bez uprzedniej zgody PKP Polskie Linie Kolejowe S.A. — są zabronione

SPIS TREŚCI

ROZDZIAŁ 1. SPORZĄDZANIE PLANÓW SCHEMATYCZNYCH POSTERUNKÓW RUCHU ORAZ PUNKTÓW EKSPEDYCYJNYCH 4

§1. Postanowienia ogólne 4

§2. Podstawy sporządzenia schematów 6

§3. Skala schematu i arkusz wydruku 6

§4. Treść schematów 7

ROZDZIAŁ 2. AKTUALIZACJA SCHEMATOW 9

§ 5. Postanowienia ogólne 9

§ 6. Wprowadzanie zmian 10

ROZDZIAŁ 3. POSTANOWIENIA KOŃCOWE 11

§ 7. Postanowienia końcowe 11

Załącznik nr 1 Budowa oznaczeń literowych 12

Załącznik nr 2 Wykaz torów 13

Załącznik nr 3 Wykaz rozjazdów 13

Załącznik nr 4 Wykaz budynków i budowli 13

Załącznik nr 5 Wykaz peronów 14

Załącznik nr 6 Tabela tytułowa 14

Załącznik nr 7 Przykładowy plan schematyczny 15

Załącznik nr 8 Znaki umowne na schematach posterunków ruchu oraz punktów ekspedycyjnych 16

ROZDZIAŁ 1. SPORZĄDZANIE PLANÓW SCHEMATYCZNYCH POSTERUNKÓW RUCHU ORAZ PUNKTÓW EKSPEDYCYJNYCH

§1. Postanowienia ogólne

1. Plan schematyczny, zwany dalej „schematem”, jest graficznym szkicem przedstawiającym na płaszczyźnie położenie kolejowych szczegółów sytuacyjnych i urządzeń technicznych, narysowanych za pomocą znaków umownych przedstawionych w Załączniku nr 8.
2. Schematy opracowuje się dla wszystkich posterunków ruchu, przystanków osobowych i bocznic kolejowych, na których znajduje się infrastruktura zarządzana przez PKP Polskie Linie Kolejowe S.A., zwana dalej „PLK SA”
3. Zarządcy infrastruktury ruchowo powiązani z infrastrukturą PLK SA którzy korzystają z infrastruktury Spółki PLK SA dostarczają w niezbędnym zakresie aktualne schematy obejmujące zarządzaną przez siebie infrastrukturę.
4. Instrukcja niniejsza ustala jednolity sposób:
   1) wykonywania schematów;
   2) aktualizacji schematów;
   3) odpowiedzialności komórek/jednostek za sporządzanie i aktualizację schematów.
5. Schematy sporządzone w myśl postanowień niniejszej instrukcji, będą wykorzystane w szczególności do celów:
   1) eksploatacyjnych (jako załącznik do regulaminów technicznych posterunków ruchu);
   2) utrzymania porządków, utrzymania budynków, instalacji i urządzeń technicznych stacji oraz utrzymania zimowego;
   3) konstrukcji rozkładu jazdy (za pomocą systemu SKRJ), nadzoru nad prowadzeniem ruchu pociągów (za pomocą systemu SEPE) oraz jako podstawa do wykonywania modeli mikro symulacyjnych ruchu kolejowego.
6. Schematy nie mogą być używane jako podkład mapowy dla opracowania projektów przebudowy i rozbudowy stacji oraz wykonywania przejść podziemnych i naziemnych.
7. Schematy należy sporządzać dla całych posterunków ruchu, przystanków osobowych i bocznic kolejowych.
8. Jeżeli na szlaku przyległym do posterunku ruchu występują tarcze ostrzegawcze odnoszące się do semafora wjazdowego, należy ująć je na schemacie wraz ze wskaźnikami W11a lub W11b.

Fragment odstępu pomiędzy tarczą ostrzegawczą, a semaforem wjazdowym należy odzwierciedlić w formie skróconej (skrócenia nie należy wykonywać na łukach), podać odległość tarczy od semafora oraz nanieść istotne dla prowadzenia ruchu kolejowego elementy infrastruktury znajdujące się na tym fragmencie (np. przejazdy kolejowo-drogowe, sygnalizatory powtarzające, tarcze ostrzegawcze przejazdowe, przystanki osobowe itp.).

9. Infrastrukturę niezarządzaną przez PLK SA należy ująć na schemacie jedynie do punktu zdawczo-odbiorczego wraz z podaniem jej nazwy oraz ze wskazaniem użytkownika lub zarządcy.
10. W przypadku, gdy w granicach posterunku ruchu lub przystanku osobowego zarządzanego przez PLK SA oraz bocznic kolejowych znajduje się infrastruktura innych użytkowników, ruchowo powiązana z infrastrukturą PLK SA (układy torowe wraz z rozjazdami i sygnalizatorami służące do prowadzenia ruchu pociągów lub manewrów, urządzenia techniczne, budowle i budynki) należy ująć je na schematach, oznaczając kolorem zielonym i opisowo ze wskazaniem kilometrażu lub punktów styku granic (np. nr rozjazdu) i nazwy zarządzającego.
11. Schemat zatwierdzany jest przez dyrektora Zakładu Linii Kolejowych podpisem w tabeli Załącznik nr 6.
12. Schematy w wersji analogowej, w tym wydruk wersji cyfrowej o ile taki został sporządzony, przechowuje się we właściwym terytorialnie Zakładzie Linii Kolejowych.
13. Nowe schematy w wersji cyfrowej będą przechowywane i udostępniane przez Moduł Dokumentacja Systemu Informacji dla Linii Kolejowych.
14. Zasady współpracy oraz zakres obowiązków i odpowiedzialności poszczególnych jednostek organizacyjnych PLK SA przy sporządzaniu i aktualizacji schematów wynikają z powierzonych im zadań.
15. Schematy należy sporządzić w postaci wektorowej z wykorzystaniem programów graficznych typu CAD, preferowany format pliku *.dwg, *.dgn
16. W ramach wykonywania prac, wywołujących zmianę (w tym także likwidację i budowę nowych) położenia kolejowych szczegółów sytuacyjnych i urządzeń technicznych, należy sporządzić nowy schemat albo jego aktualizację (jeżeli istnieje schemat zgodny z Ig-10), zgodnie z postanowieniami niniejszej instrukcji.
17. Konieczność zlecenia opracowania schematu należy uzgadniać z Biurem Nieruchomości, Geodezji i Geoinformacji.
18. Plany schematyczne objęte są Tajemnicą Przedsiębiorcy w PKP Polskie Linie Kolejowe S.A. – SZBI – Ibi – 5.

§2. Podstawy sporządzenia schematów

1. Schematy sporządza się na podstawie danych pochodzących z pomiarów bezpośrednich, map sytuacyjno-wysokościowych oraz profili podłużnych linii kolejowych. W procesie sporządzania schematu należy uwzględnić schematy urządzeń SRK oraz schematy sekcjonowania sieci trakcyjnej.
2. Przy wykonywaniu pomiarów w celu aktualizacji schematów, stosuje się najprostsze sposoby, rzutując nowe obiekty i urządzenia kolejowe na linie pomiarowe istniejące już na aktualizowanym schemacie — np.: na oś najbliższego toru, linię budynków, itp.
3. Schemat charakteryzuje się następującymi cechami:
   1) stosownym przedstawieniem treści — zgodnie ze znakami umownymi zamieszczonymi w załączniku nr 8;
   2) odpowiednim opisem schematu zamieszczonym w tabeli wykonanej zgodnie z postanowieniami niniejszej instrukcji, której wzór znajduje się w załącznikach Nr 2-6.

§3. Skala schematu i arkusz wydruku

1. Schematy opracowuje się w dwóch skalach:
   1) podłużnej (dla długości torów) — 1:2000;
   2) poprzecznej (dla wzajemnego odstępu torów) — 1:500.
2. Schemat w skali:
   1) podłużnej (dla długości torów) — 1:4000;
   2) poprzecznej (dla wzajemnego odstępu torów) — 1:1000

   może zostać zastosowany po uprzednim pozyskaniu zgody Biura Nieruchomości, Geodezji i Geoinformacji oraz właściwego miejscowo Zakładu Linii Kolejowych.
3. Schemat należy opracować w taki sposób, aby kilometracja na zobrazowaniu posterunku ruchu lub punktu eksploatacyjnego wzrastała od strony lewej do prawej.
4. Jeżeli na posterunku ruchu zbiega się kilka linii kolejowych o różnych kierunkach kilometracji, należy podać kilometraż urządzeń sterowania ruchem kolejowym według linii, do której dane urządzenie jest przypisane oraz według linii wyższej kategorii.
5. Z lewej strony arkusza, stanowiącego załącznik Nr 2-5, umieszcza się tabelę stanowiącą opis schematu zawierającą informacje dotyczące torów, rozjazdów, budynków i urządzeń stacyjnych.

6. Z prawej strony arkusza u dołu wykreśla się tabelę z opisem (metryki). Wzór metryki zawarto w załączniku Nr 6 do instrukcji.

7. Z lewej strony arkusza należy pozostawić 30 mm na wszycie.

§4. Treść schematów

1. Na schemat nanosi się następujące dane:

   1) tory:

      a) szlakowe,

      b) główne zasadnicze,

      c) główne dodatkowe,

      d) specjalnego przeznaczenia (m. in. kozły oporowe, żeberka) i boczne,

   2) punkty styku pomiędzy zarządcami;

   3) początki torów odgałęziających bocznice od torów stacyjnych (szlakowych) oraz tory zdawczo - odbiorcze obsługiwane przez PLK SA, a przy bocznicach kolejowych wszystkie tory bocznicowe.

   4) numery torów oraz w uzasadnionych przypadkach numery wstawek rozjazdowych;

   5) znaki pochyleń (załomów) profilu podłużnego torów na posterunku i przyległych szlakach na długości maksymalnej drogi hamowania przed semaforami wjazdowymi z każdego kierunku;

   6) rozjazdy, skrzyżowania torów i wykolejnice w położeniu zasadniczym, wraz z numerami, wskaźniki W17 (ukresy), urządzenia elektrycznego ogrzewania rozjazdów;

   7) górki rozrządowe, profile podłużne górek rozrządowych;

   8) sygnalizatory(semafory i tarcze) z podaniem ich opisu;

   9) wskaźniki przytorowe, strefy objęte układową kontrolą nie zajętości (odcinki torowe i zwrotnicowe), urządzenia bezpiecznej kontroli jazdy pociągu (BKJP), sygnalizatory drogowe, przytorowe urządzenia SSP, rogatki, telewizja użytkowa, hamulce torowe;

   10) przebiegi pociągowe wraz z ich opisem;

   11) granice okręgów nastawczych;

12) układ sekcjonowania sieci trakcyjnej, w tym: lokalizacja odłączników i izolatorów sekcyjnych, numeracja odłączników, pozycja odłącznika w stanie normalnym, napędy odłącznika (ręczny lub silnikowy sterowany lokalnie albo zdalnie);

13) przejazdy kolejowo - drogowe i przejścia w poziome szyn, pomieszczenia dróżników przejazdowych, strażnice;

14) budynki stacyjne (dworcowe);

15) budynki, budowle i urządzenia służące do prowadzenia ruchu kolejowego tj. takie, których wyłączenie z eksploatacji wymaga zmian w organizacji pracy posterunku ruchu albo punktu ekspedycyjnego, takie jak:

   a) mosty, wiadukty, tunele, przepusty, ściany i mury oporowe, przejścia podziemne dla pieszych, kładki dla pieszych, schody;

   b) perony i międzytorza przystosowane do wsiadania i wysiadania podróżnych, z oznaczeniem czynnych krawędzi oraz podaniem numerów,

   c) nastawnie, posterunki: zwrotniczych, stwierdzenia końca pociągu, starszego ustawiacza oraz maszynownie hamulców torowych wraz z właściwym oznaczeniem,

   d) magazyny, sortownie, rampy, place ładunkowe oznaczone kolejnymi numerami, wagi wagonowe i wozowe, dźwigi, skrajniki oraz inne handlowe urządzenia stacyjne dla odprawy i przewozu przesyłek na terenie zarządzanym przez PKP PLK S.A.,

   e) maszty i wieże GSM-R,

   f) kontenery z określeniem funkcji;

16) ulice, place i aleje, takie które znajdują się w danym okręgu, opisane zgodnie z Załącznikiem 1

17) kilometraż osi posterunku według linii głównej i pozostałych;

18) znaki kilometrowe i hektometrowe dla każdej linii osobno;

19) kilometraż dla budynków stacyjnych, nastawni, posterunków technicznych według kilometrażu linii głównej i pozostałych;

20) kilometraż przejazdów, sygnalizatorów (semafory i tarcze), liczników osi, odcinków torów izolowanych, żurawi wodnych, mostów, wiaduktów, przepustów, wskaźników oraz początków i końców peronów lub ramp;

21) kilometraż początków rozjazdów lub w przypadku rozjazdu krzyżowego jego środek, według linii do której należą oraz głównej;

22) nazwę najbliższego posterunku ruchu;

23) nazwę najbliższej stacji węzłowej;

24) w przypadku stacji węzłowych lub posterunków odgałęźnych należy oznaczyć przebieg zbiegających się linii kolejowych po torach głównych zasadniczych oraz kilometraż początku i/lub końca linii/odcinka toru według kilometrażu obu tych linii na posterunku ruchu zgodnie z instrukcją Id-12;

2. Tory i przejścia zwrotnicowe zelektryfikowane zaznacza się kolorem niebieskim.

3. Wszystkie budynki posterunków ruchu oznacza się wg zasad pokazanych w załączniku Nr 1.

4. Schematy muszą być opracowane z wykorzystaniem warstw. Minimalny zbiór warstw wraz z nazwami oraz przyporządkowaniem do nich elementów znajduje się w załączniku Nr 8.

5. Integralną częścią schematu są tabele stanowiące jego opisy umieszczone z lewej strony arkusza. Tabele zawierają następujące dane:

   1) Numer linii, numery torów, ich długość ogólną, budowlaną i użyteczną, w przypadku torów nieelektryfikowanych informacja o tym; (Załącznik Nr 2);

   2) Numer linii, numery rozjazdów, długość, typ, kilometry ich początku lub środka, (wg odpowiedniej linii); numery i lokalizacja wykolejnic (Załącznik Nr 3);

   3) Numery i przeznaczenie budynków - w tym kontenery (Załącznik Nr 4);

   4) Perony - numer linii, długość użyteczna krawędzi dla każdego kierunku jazdy, szerokość i wysokość krawędzi peronu nad główka szyny oraz odległości osi torów od krawędzi peronowych (Załącznik Nr 5).

ROZDZIAŁ 2. AKTUALIZACJA SCHEMATOW

§ 5. Postanowienia ogólne

1. Schematy zmienia i uzupełnienia Zakład Linii Kolejowych.

2. Zmiany i uzupełnienia do schematów zgłaszane są do Zakładu Linii Kolejowych przez Sekcję Eksploatacji - wszystkie zgłaszane zmiany i uzupełnienia są ewidencjonowane.

3. Zakład Linii Kolejowych po wprowadzeniu zmian na schemacie, sporządza i przekazuje kopie dla sekcji eksploatacji.

§ 6. Wprowadzanie zmian

W przypadku dokonywania zmian w schemacie obowiązuje następujący tryb postępowania:

1) podmiot, który zamierza dokonać zmian przed przystąpieniem do robót przesyła do Zakładu Linii Kolejowych kopie zatwierdzonego projektu przebudowy lub budowy z opisem projektowanych zmian;

2) na podstawie dostarczonego projektu Zakład Linii Kolejowych sporządza potrzebną ilość roboczych odbitek schematów, na których podmiot wnosi kolorem czerwonym projektowane zmiany, a kolorem żółtym elementy do demontażu, likwidacji;

3) do czasu wymiany schematu na aktualny, w regulaminach technicznych znajduje się uaktualniona robocza odbitka schematu z opisem uaktualnienia;

4) w przypadku budowy, przebudowy, modernizacji posterunku ruchu lub punktów ekspedycyjnych (lub ich części) komplet schematów powinien być dostarczony do Zakładu Linii Kolejowych w terminach określnych w §4 ust. 6 punkt 1, 2 Instrukcji o sporządzaniu regulaminów technicznych lr-3;

5) za aktualność dokumentacji technicznej oraz dokumentacji urządzeń srk dołączonej do regulaminów technicznych odpowiada Naczelnik Sekcji Eksploatacji;

6) zgodność aktualnego schematu z sytuacją na gruncie należy skontrolować przynajmniej raz w roku oraz potwierdzić datą i podpisem przez Naczelnika Sekcji Eksploatacji lub jego Zastępcę, głównego inżyniera ds. automatyki.

7) Sekcja Eksploatacji sporządza wykaz wniesionych poprawek na schemacie wraz z opisem. Wykaz ten stanowi załącznik do uaktualnionego schematu;

8) Dyrektor Zakładu Linii Kolejowych zatwierdza nowy lub aktualizowany schemat;

9) Zakład Linii Kolejowych, po wprowadzeniu zmian na schemacie umieszcza na nim klauzulę - pieczątkę (stempel) wg poniższego wzoru;

Stan z dnia……. Schemat uzupełnił dnia..... (podpis czytelny) Sprawdził dnia..... (podpis czytelny) Zatwierdził dnia..... (podpis czytelny)

10) Zakład Linii Kolejowych przesyła schemat do Biura Nieruchomości, Geodezji i Geoinformacji w celu zdeponowania w Module Dokumentacja Systemu Informacji dla Linii Kolejowych;

11) wycofane, nieaktualne odbitki schematów, Zakład Linii Kolejowych przechowuje zgodnie z postanowieniami Instrukcji Kancelaryjnej la-1.

ROZDZIAŁ 3. POSTANOWIENIA KOŃCOWE

§ 7. Postanowienia końcowe

1. Zakłady Linii Kolejowych są zobowiązane do sukcesywnego zastępowania schematów analogowych, schematami wektorowymi.
2. Schematy sporządzone przed wejściem w życie niniejszej instrukcji stosuje się na zasadach dotychczasowych do czasu zastąpienia schematu, o którym mowa w niniejszej instrukcji.
3. Podmiot wykonujący zmiany w terenie informuje Zakład Linii Kolejowych o wszelkich zmianach w obiektach wymienionych w § 4 niniejszej instrukcji.
4. Zakład Linii Kolejowych zobowiązany jest do precyzyjnego określenia zasięgu infrastruktury, dla której nowy plan schematyczny będzie sporządzany.
5. Zakład Linii Kolejowych zobowiązany jest do naniesienia na schemacie wszystkich obiektów wymienionych w § 4 niniejszej instrukcji.
6. Podmiot będący użytkownikiem, władającym lub zarządzającym budynkami, budowlami oraz urządzeniami oznaczonymi w § 4 niniejszej instrukcji ma obowiązek przekazania do Zakładu Linii Kolejowych- informacji dotyczącej zmian w zakresie treści schematu.

Załącznik nr 1 Budowa oznaczeń literowych

LP.	SPOSÓB BUDOWY OZNACZENIA LITEROWEGO	OZNACZENIA
1	Kierunek linii: oznacza się pełnymi nazwami sąsiednich posterunków ruchu z tym, że: a) nazwy stacji węzłowych umieszcza się w nawiasach kwadratowych b) nazwy przyległych posterunków następczych umieszcza się w nawiasach zwykłych.	[Tulipan] (Wygoda)
2	Budynki nastawni: a) nastawnia dysponująca np. na stacji Jawor zaleca się aby druga litera opisu była spółgłoską b) przy większej liczbie nastawni dysponujących dodaje się kolejne duże litery alfabetu c) nastawnie wykonawcze oznacza się skrótem nastawni dysponującej i kolejną liczbą	Jr JrA, JrB Jr1, JrA1
3	Ulice, aleje, place: a) nazwy ulic - zastosowanie skrótu "ul." oraz druga część nazwa własna b) nazwy alei - zastosowanie skrótu "al." oraz druga część nazwa własna c) nazwy placu - zastosowanie skrótu "pl." oraz druga część nazwa własna	ul. Złota al. Solidarności pl. Wilsona
4	Przebiegi: a) w celu bliższego określenia przebiegów, np. na semafor D, indeksy umieszcza się w górnej części oznaczenia. b) w celu określenia toru lub kierunku np. sygnalizowane semaforem M, indeksy umieszcza się w dolnej części oznaczenia.	D^2 M_s

Załącznik nr 2 Wykaz torów

WYKAZ TORÓW												
Nr linii	Nr toru	Przeznaczenie toru	Długość ogólna			Długość budowlana			Długość użyteczna toru			Zarządca / użytkownik
			od	do	[m]	od	do	[m]	od	do	[m]	

* W przypadku długości ogólnej, budowlanej oraz użytecznej toru należy zastosować się do definicji zawartej w Rozporządzeniu Ministra Transportu i Gospodarki Morskiej z dnia 10 września 1998 r. w sprawie warunków technicznych, jakim powinny odpowiadać budowle kolejowe i ich usytuowanie. Dział I – Przepisy ogólne par. 3.

Załącznik nr 3 Wykaz rozjazdów

WYKAZ ROZJAZDÓW												
Nr linii	Nr rozjazdu	Charakterystyka techniczna rozjazdu						Lokalizacja				Zarządca / Użytkownik
								zwyczajny		UR		
		Rodzaj	Kierunek	Typ	Skos	Promień [m]	Długość [m]	PR [km]	KR [km]	zwyczajny [km]	krzyżowy [km] / [km]	
								krzyżowy SR [km]				

* Zastosowane skróty: PR- początek rozjazdu; KR – koniec rozjazdu; SR – środek rozjazdu; UR - ukres.

Załącznik nr 4 Wykaz budynków i budowli

WYKAZ BUDYNKÓW I BUDOWLI			
Nr budynku / budowli	Przeznaczenie budynku / budowli	Km osi budynku / budowli	Uwagi

* Zgodnie z $4 ust.1 pkt. 15 z wyłączeniem podpunktu a)

Załącznik nr 5 Wykaz peronów

WYKAZ PERONÓW										
Nr linii	Nr peronu	Lokalizacja peronu		Długość użyteczna krawędzi		Wysokość peronu nad główką szyny		Odległość osi torów od krawędzi peronowych		Szerokość peronu
		PP [km]	KP [km]	lewa	prawa	lewa	prawa	lewa	prawa	

* Zastosowane skróty: PP – początek peronu; KP – koniec peronu;

Załącznik nr 6 Tabela tytułowa

	Data	Nazwisko	Podpis	**PKP Polskie Linie Kolejowe S.A.**
Opracował				
Wykreślił				Zakład Linii Kolejowych
Zatwierdził				w ……..
Skala 1:2000 1:500	Plan schematyczny ……			Stan na dzień ……

Załącznik nr 7 — Przykładowy plan schematyczny (wymiary 420x3000)

WYKAZ TORÓW

Nr linii	Nr toru	Przeznaczenie toru	Długość ogólna					Długość budowlana					Długość użyteczna toru			Zarządca /Użytkownik
			od		do		[m]	od		do		[m]	od	do	[m]	
2	1a	główny zasadniczy	KRz	2	PRz	20	1094	KRz	2	PRz	20	895	l.o.	sem. J1	599	PKP Polskie Linie Kolejowe Zakład Linii Kolejowych w Siedlcach
													l.o.	sem. F1	596	
2	1b	główny zasadniczy	KRz	20	PRz	48	1116	KRz	20	PRz	48	949	l.o.	sem. R1	595	
													l.o.	sem. L1	562	
2	2a	główny zasadniczy	PRz	1	PRz	22	1246	PRz	1	PRz	22	1050	l.o.	sem. K2	675	
													l.o.	sem. G2	671	
2	2b	główny zasadniczy	KRz	22	KRz	47	1050	KRz	22	KRz	47	842	l.o.	sem. P2	527	
													l.o.	sem. L2	701	
2	3	główny dodatkowy	PRz	12	PRz	20	742	PRz	12	PRz	20	626	l.o.	sem. J3	530	
													l.o.	sem. F3	526	
2	3a	boczny	PRz	19	k.op.	-	66	PRz	19	k.op.	-	33	-	-	-	
31	4a	główny zasadniczy	PRz	6	KRz	21	849	PRz	6	KRz	21	690	l.o.	sem. K4	525	
													l.o.	sem. G4	541	
31	4b	główny zasadniczy	PRz	21	KRz	51	1264	PRz	21	KRz	51	1031	l.o.	sem. P4	563	
													l.o.	sem. L4	565	
2	5a	główny dodatkowy	PRz	10	PRz	14	508	PRz	10	PRz	14	358	l.o.	Tm 21	282	
													l.o.	sem. F5	237	
2	5b	główny dodatkowy	PRz	14	PRz	38	997	PRz	14	PRz	38	914	l.o.	sem. R5	759	
													l.o.	sem. M5	759	
2	6a	główny dodatkowy	PRz	9	KRz	15	353	PRz	9	KRz	15	270	l.o.	Tm 6	221	
													l.o.	sem. G6	119	
2	6b	główny dodatkowy	PRz	15	PRz	36	1144	PRz	15	PRz	36	986	l.o.	sem. P6	811	
													l.o.	sem. N6	811	
2	7	główny dodatkowy	PRz	14	PRz	40	1103	PRz	14	PRz	40	912	l.o.	sem. R7	760	
													l.o.	sem. M7	761	
2	8	główny dodatkowy	PRz	15	PRz	34	1050	PRz	15	PRz	34	934	l.o.	sem. P8	774	
													l.o.	sem. N8	775	
2	10	główny dodatkowy	PRz	8	k.op.	-	370	PRz	8	k.op.	-	287	l.o.	sem. H10	221	
													l.o.	sem. G10	221	
2	41	boczny, niezelektryfikowany	PRz	301	obrotnica		189	PRz	301	obrotnica		156	-	-	-	
2	43	boczny, niezelektryfikowany	KRz	302	obrotnica		235	KRz	302	obrotnica		180	-	-	-	
2	45	boczny, niezelektryfikowany	k.op	-	obrotnica		62	k.op	-	obrotnica		58	-	-	-	
2	91b	boczny, niezelektryfikowany	PRz	316	PRz	318	223	PRz	316	PRz	318	139	U Rz 316	PRz 317	133	
2	93	boczny, niezelektryfikowany	PRz	316	PRz	318	223	PRz	316	PRz	318	165	U Rz 316	U Rz 318	157	
2	100	boczny, niezelektryfikowany	PRz	17	PRz	32	903	PRz	17	PRz	32	837	l.o.	Tm 100	778	
													l.o.	Tm 10	777	
2	101a	boczny, niezelektryfikowany	PRz	13	PRz	312	626	PRz	13	PRz	312	532	U Rz 312	Tm 23	508	
2	101b	boczny, niezelektryfikowany	KRz	312	PRz	37	394	KRz	312	PRz	37	294	U Rz 312	Tm 31	210	
2	101c	boczny, niezelektryfikowany	PRz	313	KRz	316	519	PRz	313	KRz	316	430	Tm 32	U Rz 314	210	
2	102	boczny, niezelektryfikowany	PRz	18	PRz	31	818	PRz	18	PRz	31	752	l.o.	Tm 102	693	
													l.o.	Tm 12	695	
2	103a	boczny, niezelektryfikowany	p.m.	311	k.op.	-	413	p.m.	311	k.op.	-	398	U Rz 311	k.op.	373	
2	103b	boczny, niezelektryfikowany	p.m.	311	PRz	315	583	p.m.	311	PRz	315	539	U Rz 311	U Rz 314	501	
2	104	boczny, niezelektryfikowany	PRz	16	PRz	35	1047	PRz	16	PRz	35	814	l.o.	Tm 104	695	
													l.o.	Tm 14	696	
2	105	boczny, niezelektryfikowany	PRz	310	k.op.	-	330	PRz	310	k.op.	-	265	U Rz 305	k.op.	198	
2	107	boczny, niezelektryfikowany	PRz	303	PRz	305	250	PRz	303	PRz	305	163	U Rz 303	U Rz 304	107	
2	109	boczny, niezelektryfikowany	PRz	302	PRz	304	334	PRz	302	PRz	304	246	U Rz 303	U Rz 304	125	
2	111	boczny, niezelektryfikowany	PRz	302	PRz	309	407	PRz	302	PRz	309	353	U Rz 302	U Rz 309	313	
2	113	boczny, niezelektryfikowany	PRz	308	k.op.	-	102	PRz	308	k.op.	-	75	U Rz 308	k.op.	75	
2	115	boczny, niezelektryfikowany	PRz	307	k.op.	-	196	PRz	307	k.op.	-	168	U Rz 307	k.op.	155	
2	117	boczny, niezelektryfikowany	PRz	312	gr. PKP		358	PRz	312	gr. PKP		177	-	-	-	
2	121	boczny, niezelektryfikowany	PRz	317	k.op.	-	255	PRz	317	k.op.	-	227	U Rz 317	k.op.	209	
2	123	boczny, niezelektryfikowany	PRz	318	brama		130	PRz	318	brama		102	U Rz 317	brama	5	
2	201	boczny	KRz	201	PRz	11	833	KRz	201	PRz	11	657	l.o.	Tm 201	330	
2	203	boczny	PRz	203	PRz	206	402	PRz	203	PRz	206	348	l.o.	Tm 203	288	
2	205	boczny	PRz	204	PRz	205	319	PRz	204	PRz	205	258	l.o.	Tm 205	201	
2	207	boczny, niezelektryfikowany	PRz	202	PRz	3	535	PRz	202	PRz	3	354	l.o.	Tm 207	201	
2	209	boczny, nieczynny	PRz	209	k.op.	-	337	PRz	209	k.op.	-	236	U Rz 208	k.op.	155	
2	211	boczny, niezelektryfikowany	PRz	208	k.op.	-	113	PRz	208	k.op.	-	86	U Rz 201	k.op.	79	
2	301	boczny, niezelektryfikowany	PRz	39	k.op.	-	424	PRz	39	k.op.	-	391	Tm 301	k.op.	334	
2	302a	boczny, niezelektryfikowany	PRz	33	PRz	49	483	PRz	33	PRz	49	416	l.o.	Tm 402	365	
													l.o.	Tm 401	365	
2	302b	boczny, niezelektryfikowany	PRz	44	PRz	407	620	PRz	44	PRz	407	493	Tm 43	U Rz 406	330	
2	304	boczny, niezelektryfikowany	PRz	403	k.op.	-	518	PRz	403	k.op.	-	485	U Rz 403	k.op.	435	
2	306	boczny, niezelektryfikowany	PRz	406	k.op.	-	560	PRz	406	k.op.	-	500	U Rz 403	k.op.	435	
2	308	boczny, niezelektryfikowany	PRz	401	PRz	402	529	PRz	401	PRz	402	475	U Rz 401	U Rz 402	470	
2	310a	boczny, niezelektryfikowany	PRz	401	k.op.	-	265	PRz	401	k.op.	-	265	k.op.	PRz 401	245	
2	310b	boczny, niezelektryfikowany	PRz	401	PRz	407	670	PRz	401	PRz	407	549	U Rz 401	U Rz 402	470	
2	312	boczny, niezelektryfikowany	PRz	404	k.op.	-	512	PRz	404	k.op.	-	479	U Rz 404	k.op.	298	
2	314	boczny, niezelektryfikowany	PRz	405	k.op.	-	309	PRz	405	k.op.	-	244	U Rz 404	k.op.	172	
2	501	boczny, niezelektryfikowany	PRz	51	Wk	42	56	PRz	51	Wk	42	23	-	-	-	
2	601	boczny, niezelektryfikowany	PRz	201	k.op.	-	57	PRz	201	k.op.	-	30	U Rz 201	k.op.	12	
2	603	boczny, niezelektryfikowany	PRz	201	k.op.	-	160	PRz	201	k.op.	-	133	Wk	k.op.	103	
2	5001	wstawka	PRz	1	PRz	2	95	PRz	1	PRz	2	12	-	-	-	
2	5004	wstawka	PRz	4	PRz	5	95	PRz	4	PRz	5	12	-	-	-	
2	5021	wstawka	PRz	21	PRz	22	101	PRz	21	PRz	22	18	-	-	-	
2	5041	wstawka	PRz	41	PRz	43	95	PRz	41	PRz	43	12	-	-	-	
2	5042	wstawka	PRz	42	PRz	45	102	PRz	42	PRz	45	19	-	-	-	
2	5046	wstawka	PRz	46	PRz	48	95	PRz	46	PRz	48	12	-	-	-	
2	5047	wstawka	PRz	47	PRz	50	102	PRz	47	PRz	50	19	-	-	-	

WYKAZ ROZJAZDÓW

Nr linii	Nr rozjazdu	Charakterystyka techniczna rozjazdu						Lokalizacja rozjazdu			Zarządca /Użytkownik
		Rodzaj	Kierunek	Typ	Skos	Promień [m]	Długość [m]	PR [km]	KR [km]	UR [km]	
2	1	Rz	P	60E1	1:12	500	41,59	92,073	92,115	92,140	PKP Polskie Linie Kolejowe Zakład Linii Kolejowych w Siedlcach
2	2	Rz	P	60E1	1:12	500	41,59	92,168	92,126	92,101	
2	3	Rz	L	60E1	1:9	300	33,23	92,216	92,183	92,161	
2	4	Rz	L	60E1	1:12	500	41,59	92,241	92,283	92,308	
2	5	Rz	L	60E1	1:12	500	41,59	92,336	92,294	92,269	
2	6	Rz	L	60E1	1:12	500	41,59	92,381/-0,313	92,423	92,448	
31	7	Rz	P	60E1	1:9	300	33,23	92,475/-0,218	-0,251	-0,273	
31	8	Rz	P	60E1	1:12	500	41,59	92,486/-0,208	-0,166	-0,141	
2	9	Rz	P	60E1	1:12	500	41,59	92,537	92,579	92,604	
2	10	Rz	P	60E1	1:12	500	41,59	92,381	92,423	92,448	
2	11	Rz	L	60E1	1:9	300	33,23	92,468	92,435	92,413	
2	12	Rz	P	60E1	1:12	500	41,59	92,479	92,521	92,546	
2	13	Rz	P	60E1	1:9	300	33,23	92,845	92,878	92,900	
2	14	Rz	P	60E1	1:12	500	41,59	92,888	92,930	92,955	
2	15	Rz	L	60E1	1:12	500	41,59	92,848	92,890	92,915	
2	16	Rz	L	60E1	1:9	300	33,23	92,899	92,932	92,954	
2	17	Rz	P	49E1	1:9	300	33,23	92,942	92,975	92,997	
2	18	Rz	P	49E1	1:9	300	33,23	92,984	93,017	93,039	
2	19	Rz	P	60E1	1:9	300	33,23	93,133	93,166	93,188	
2	20	Rz	L	60E1	1:12	500	41,59	93,221	93,179	93,154	
31	21	Rz	P	60E1	1:12	500	41,59	93,187/0,493	0,535	0,560	
2	22	Rz	P	60E1	1:12	500	41,59	93,288	93,246	93,221	
2	31	Rz	L	49E1	1:9	300	33,23	93,799	93,766	93,744	
2	32	Rz	L	49E1	1:9	300	33,23	93,841	93,808	93,786	
2	33	Rz	L	49E1	1:9	300	33,23	93,859	93,892	93,914	
2	34	Rz	P	60E1	1:12	500	41,59	93,894	93,852	93,827	
2	35	Rz	P	60E1	1:9	300	33,23	93,937	93,904	93,882	
31	36	Rz	P	60E1	1:12	500	41,59	93,989/1,296	1,254	1,229	
2	37	Rld	D	60E1	1:9	300	33,23	93,828	93,795	93,773	
2	38	Rz	P	60E1	1:12	500	41,59	93,844	93,802	93,777	
2	39	Rz	P	60E1	1:9	300	33,23	93,897	93,930	93,952	
2	40	Rz	L	60E1	1:12	500	41,59	93,989	93,947	93,922	
2	41	Rz	L	60E1	1:12	500	41,59	94,033	94,075	94,100	
31	42	Rz	P	60E1	1:12	500	41,59	94,082/1,388	1,430	1,455	
2	43	Rz	L	60E1	1:12	500	41,59	94,128	94,086	94,061	
31	44	Rz	L	60E1	1:9	300	33,23	94,156/1,461	1,494	1,516	
2	45	Rz	P	60E1	1:12	500	41,59	94,184	94,142	94,117	
2	46	Rz	P	60E1	1:12	500	41,59	94,200	94,242	94,267	
2	47	Rz	L	60E1	1:12	500	41,59	94,257	94,299	94,324	
2	48	Rz	P	60E1	1:12	500	41,59	94,295	94,253	94,228	
2	49	Rz	P	49E1	1:9	300	33,23	94,338	94,305	94,283	
31	50	Rz	L	60E1	1:12	500	41,59	94,359/1,666	1,624	1,599	
31	51	Rz	P	60E1	1:9	300	33,23	94,417/1,724	1,757	1,779	
2	201	Rz	L	S49	1:9	190	27,14	91,663	91,636	91,614	
2	202	Rz	P	49E1	1:9	190	27,14	91,683	91,710	91,732	
2	203	Rz	P	49E1	1:9	190	27,14	91,724	91,751	91,773	
2	204	Rz	L	49E1	1:9	190	27,14	91,771	91,798	91,820	
2	205	Rz	P	49E1	1:9	300	33,23	92,088	92,055	92,033	
2	206	Rz	P	49E1	1:9	190	27,14	92,098	92,071	92,049	
2	207	Rkpd	x	49E1	1:9	190	33,23	92,157		92,118 / 92,196	
2	208	Rz	L	49E1	1:9	190	27,14	92,265	92,238	92,216	
2	209	Rz	L	49E1	1:9	190	27,14	92,335	92,308	92,286	
2	301	Rz	L	49E1	1:9	300	33,23	92,919	92,886	92,864	
2	302	Rz	L	S42	1:9	205	28,10	92,913	92,941	92,963	
2	303	Rz	L	S49	1:9	300	33,23	93,037	93,070	93,092	
2	304	Rz	L	S49	1:9	190	27,14	93,244	93,217	93,195	
2	305	Rz	L	S49	1:9	190	27,14	93,270	93,243	93,221	
2	307	Rz	L	S49	1:9	190	27,14	93,196	93,169	93,147	
2	308	Rz	P	S49	1:9	190	27,14	93,271	93,244	93,222	
2	309	Rz	L	60E1	1:9	190	27,14	93,317	93,290	93,268	
2	310	Rz	L	UIC60	1:9	300	33,23	93,357	93,324	93,302	
2	311	Rkpd	x	S49	1:9	190	33,23	93,414		93,375 / 93,453	
2	312	Rz	L	49E1	1:9	300	33,23	93,471	93,438	93,416	
2	313	Rz	L	49E1	1:9	300	33,23	93,692	93,725	93,747	
2	314	Rz	L	S49	1:9	190	27,14	93,997	93,970	93,948	
2	316	Rz	L	S42	1:9	205	28,10	94,183	94,211	94,233	
2	317	Rz	P	S42	1:9	205	28,10	94,346	94,374	94,396	
2	318	Rz	L	S42	1:9	205	28,10	94,406	94,378	94,356	
2	401	Rz	P	S49	1:9	190	27,14	94,080	94,107	94,129	
2	402	Rz	L	S49	1:9	190	27,14	94,624	94,597	94,575	
2	403	Rz	L	UIC60	1:9	300	33,23	94,667	94,634	94,612	
2	404	Rz	L	UIC60	1:9	300	33,23	94,634	94,601	94,579	
2	405	Rz	P	UIC60	1:9	300	33,23	94,701	94,668	94,646	
2	406	Rz	P	UIC60	1:9	190	27,14	94,706	94,679	94,657	
2	407	Rz	L	UIC60	1:9	300	33,23	94,754	94,721	94,699	
2	408	Rz	L	49E1	1:9	190	27,14	94,570	94,543	94,521	
2	409	Rz	P	49E1	1:9	190	27,14	94,781	94,754	94,732	
2	410	Rz	P	60E1	1:9	300	33,23	94,812	94,779	94,757	
2	411	Rz	P	49E1	1:9	190	27,14	94,816	94,789	94,767	
2	412	Rz	L	60E1	1:9	190	27,14	94,634	94,607	94,585	
2	413	Rz	P	60E1	1:9	300	33,23	94,878	94,845	94,823	
2	601	Rz	P	60E1	1:9	300	33,23	95,031	94,998	94,976	


118.580
Repki
118.680
◎ 118.6
◎ 118.7
[Mińsk

WYKAZ BUDYNKÓW I BUDOWLI

Nr budynku	Przeznaczenie budynku	Km osi budynku	Uwagi
1	Budynek nastawni "Si"	92,516	-
2	Budynek stacyjny	92,694	-
3	Kontener SRK	95,438	-
4	Wieża GSM-R	92,240	-
5	Kontener przy wieży GSM-R	-	-
6	Obrotnica	-	-
7	Budynek ISE	92,748	-
8	Budynek ZLK	92,701	-
9	Budynek CPN	-	-

WYKAZ PERONÓW

Nr linii	Nr peronu	Lokalizacja peronu		Długość użyteczna krawędzi [m]		Wysokość peronu nad główką szyny [cm]		Odległość osi torów od krawędzi peronowych [m]		Szerokość peronu [m]
		PP [km]	KP [km]	lewa	prawa	lewa	prawa	lewa	prawa	
2	1	92,618	92,818	-	200	-	55	-	1,725	8,00
2	2	92,644	93,044	400	400	76	76	1,725	1,725	10,20
2	3	92,644	93,044	400	400	76	76	1,725	1,725	10,20

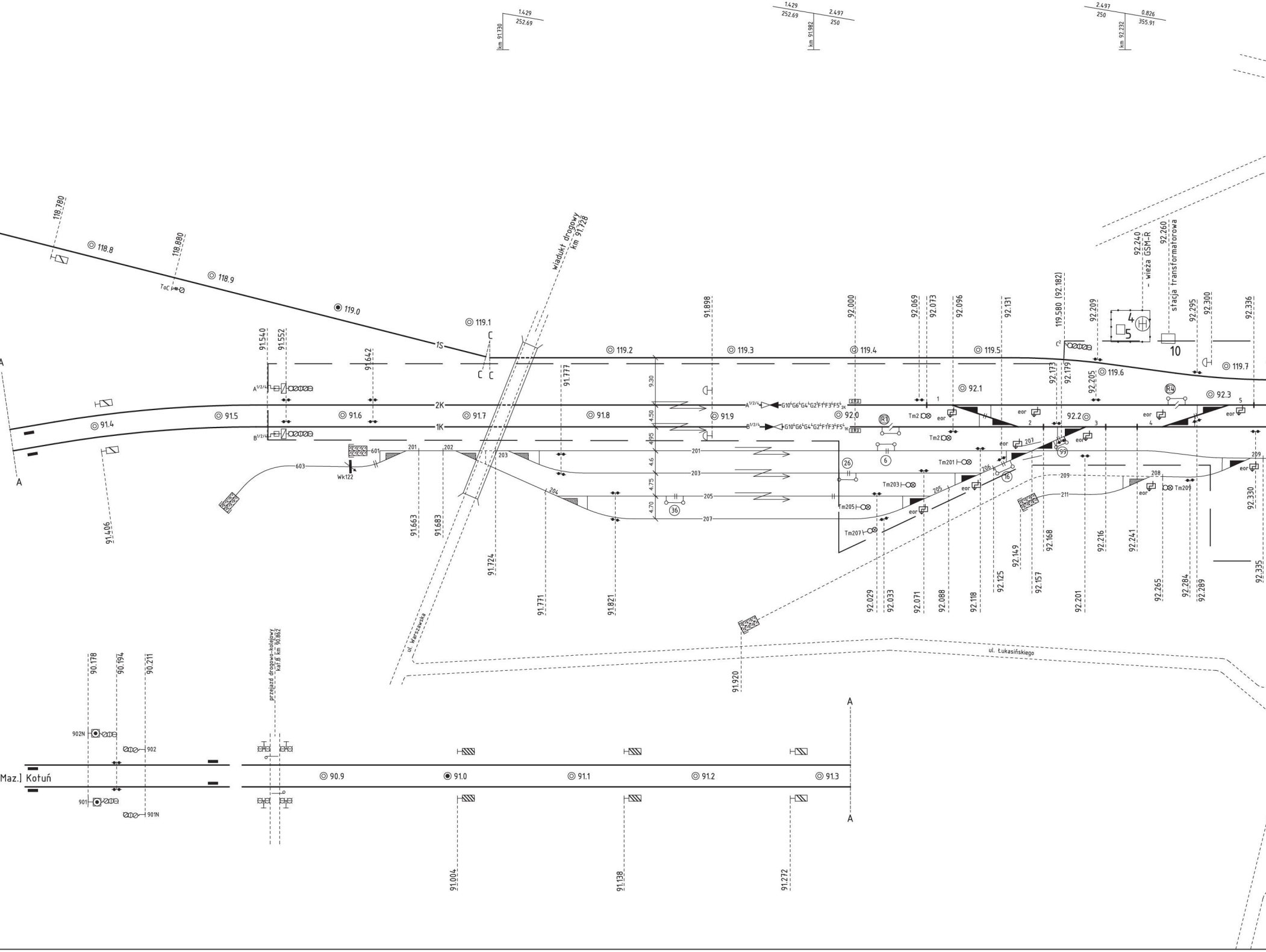
km 91.730
1.429
252.69
km 91.982
1.429
252.69
2.497
250
km 92.232
2.497
250
0.826
355.91
118.780
◎ 118.8
118.880
ToC
◎ 118.9
● 119.0
◎ 119.1
1S
wiadukt drogowy km 91.728
C
C C
91.540
91.552
91.642
91.777
91.898
92.000
92.069
92.073
92.096
92.131
119.580 (92.182)
92.209
92.240 - wieża GSM-R
92.260 stacja transformatorowa
92.295
92.300
92.336
◎ 119.2
◎ 119.3
◎ 119.4
◎ 119.5
◎ 119.6
◎ 119.7
C²
4
5
10
92.173
92.179
92.205
R4
◎ 92.1
◎ 92.3
◎ 92.0
92.2 ◎
A
A^{1/2/4}
B^{1/2/4}
2K
1K
G10⁴G6⁴G4⁴G2⁴F1⁴F3⁴F5⁴2K
G10⁴G6⁴G4⁴G2⁴F1⁴F3⁴F5⁴1K
9.30
4.50
4.95
4.6
4.75
4.70
◎ 91.4
◎ 91.5
◎ 91.6
◎ 91.7
◎ 91.8
◎ 91.9
R1
Tm2
Tm2
eor
1
2
3
4
5
207
99
16
206
209
201
203
205
207
208
209
211
26
6
36
601
603
Wk122
202
204
Tm201
Tm203
Tm205
Tm207
Tm209
A
91.406
91.663
91.683
91.724
91.771
91.821
92.029
92.033
92.071
92.088
92.118
92.125
92.149
92.157
92.168
92.201
92.216
92.241
92.265
92.284
92.289
92.330
92.335
ul. Warszawska
91.920
ul. Łukasińskiego
90.178
90.194
90.211
przejazd drogowo-kolejowy kat.B km 90.862
902N
902
901
901N
Maz.] Kotuń
◎ 90.9
● 91.0
◎ 91.1
◎ 91.2
◎ 91.3
A
A
91.004
91.138
91.272

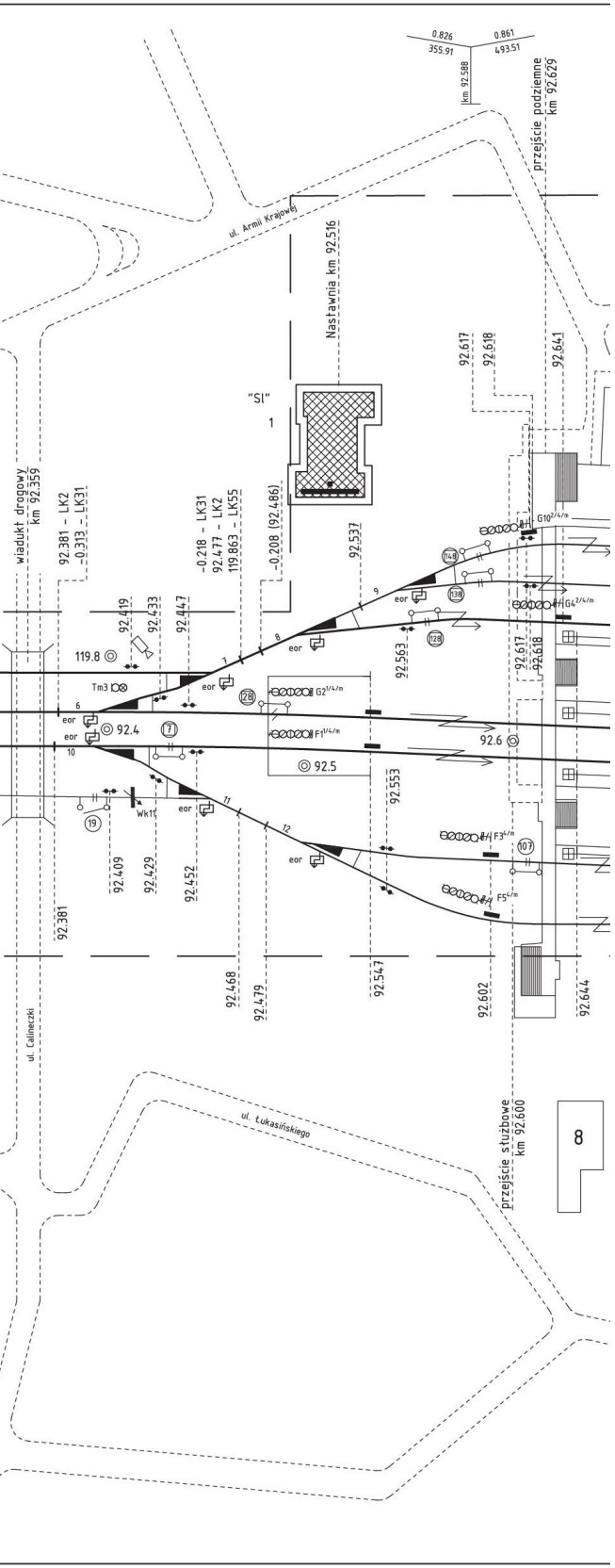

0.826
355.91
0.861
493.51
km 92.588
przejście podziemne km 92.629
ul. Armii Krajowej
Nastawnia km 92.516
"Sl"
1
92.617
92.618
92.641
wiadukt drogowy km 92.359
92.381 - LK2
-0.313 - LK31
-0.218 - LK31
92.477 - LK2
119.863 - LK55
-0.208 (92.486)
92.537
G10
14
13
G4
12
eor
9
8
7
6
10
11
12
92.419
92.433
92.447
92.563
92.617
92.618
119.8
Tm3
G2
F1
92.4
92.5
92.6
7
19
Wk1
F3
F5
10
92.553
92.409
92.429
92.452
92.381
92.468
92.479
92.547
92.602
92.644
ul. Calineczki
ul. Łukasińskiego
przejście służbowe km 92.600
8

Załącznik nr 8 Znaki umowne na schematach posterunków ruchu oraz punktów ekspedycyjnych

Oś toru głównego na liniach normalnotorowych i wąskotorowych		
NAZWA WARSTWY	układ torowy	
ATRYBUTY GRAFICZNE	UWAGI	
—— 1 ——		
ELEMENTY PRZEDSTAWIENIA GRAFICZNEGO		
ELEMENT	OPIS ELEMENTU	WYMIARY [mm]
——	grubość linii	0.5
1	tekst	2.5

Oś toru bocznego na liniach normalnotorowych i wąskotorowych		
NAZWA WARSTWY	układ torowy	
ATRYBUTY GRAFICZNE	UWAGI	
—— 8 ——		
ELEMENTY PRZEDSTAWIENIA GRAFICZNEGO		
ELEMENT	OPIS ELEMENTU	WYMIARY [mm]
——	grubość linii	0.35
8	tekst	2.5

Oś toru na liniach szerokotorowych		
NAZWA WARSTWY	układ torowy	
ATRYBUTY GRAFICZNE	UWAGI	
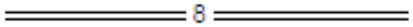		
ELEMENTY PRZEDSTAWIENIA GRAFICZNEGO		
ELEMENT	OPIS ELEMENTU	WYMIARY [mm]
	grubość linii odstęp a	0.35 0.4
8	tekst	1.8

Tor kolejowy normalny i wąski wzajemnie splecione (splot torów)		
NAZWA WARSTWY	układ torowy	
ATRYBUTY GRAFICZNE	UWAGI	
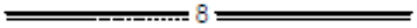		
ELEMENTY PRZEDSTAWIENIA GRAFICZNEGO		
ELEMENT	OPIS ELEMENTU	WYMIARY [mm]
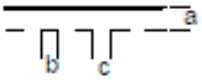	grubość linii odstęp a kreska b odstęp c	0.35 0.4 1 1
8	tekst	1.8

Oś toru rozebranego / nieczynnego		
NAZWA WARSTWY	układ torowy	
ATRYBUTY GRAFICZNE	UWAGI	
ELEMENTY PRZEDSTAWIENIA GRAFICZNEGO		
ELEMENT	OPIS ELEMENTU	WYMIARY [mm]
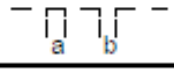	grubość linii kreska a odstęp b	0.35 2 1

Istniejące podtorze		
NAZWA WARSTWY	układ torowy	
ATRYBUTY GRAFICZNE	UWAGI	

ELEMENTY PRZEDSTAWIENIA GRAFICZNEGO		
ELEMENT	OPIS ELEMENTU	WYMIARY [mm]
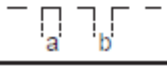	grubość linii kreska a odstęp b	0.18 1 1

Rozjazd zwyczajny ze zwrotnicą uzależnioną		
NAZWA WARSTWY	układ torowy	
ATRYBUTY GRAFICZNE	UWAGI	
 	Zasadnicze położenie na tor główny. Zasadnicze położenie na tor odgałęźny.	
ELEMENTY PRZEDSTAWIENIA GRAFICZNEGO		
ELEMENT	OPIS ELEMENTU	WYMIARY [mm]
	grubość linii początku rozjazdu kreska a odstęp b odstęp c	0.18 2 1 1
12	tekst	1.8

Rozjazd zwyczajny ze zwrotnicą nieuzależnioną		
NAZWA WARSTWY	układ torowy	
ATRYBUTY GRAFICZNE	UWAGI	
		
ELEMENTY PRZEDSTAWIENIA GRAFICZNEGO		
ELEMENT	OPIS ELEMENTU	WYMIARY [mm]
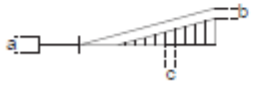	grubość linii początku rozjazdu kreska a odstęp b odstęp c grubość linii pionowych	0.18 2 1 1 0.18
12	tekst	1.8

Rozjazd zwyczajny nieoddany do użytku		
NAZWA WARSTWY	układ torowy	
	UWAGI	
		
ELEMENTY PRZEDSTAWIENIA GRAFICZNEGO		
ELEMENT	OPIS ELEMENTU	WYMIARY [mm]
	grubość linii początku rozjazdu kreska a odstęp b	0.18 2 1
12	tekst	1.8

Rozjazd łukowy jednostronny ze zwrotnicą uzależnioną		
NAZWA WARSTWY	układ torowy	
ATRYBUTY GRAFICZNE	UWAGI	
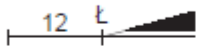		
ELEMENTY PRZEDSTAWIENIA GRAFICZNEGO		
ELEMENT	OPIS ELEMENTU	WYMIARY [mm]
	grubość linii początku rozjazdu kreska a odstęp b	0.18 2 1
12	tekst	1.8

Rozjazd łukowy dwustronny ze zwrotnicą uzależnioną		
NAZWA WARSTWY	układ torowy	
ATRYBUTY GRAFICZNE	UWAGI	
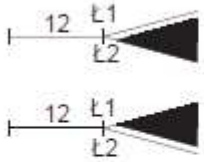	Zasadnicze położenie na tor lewy. Zasadnicze położenie na tor prawy.	
ELEMENTY PRZEDSTAWIENIA GRAFICZNEGO		
ELEMENT	OPIS ELEMENTU	WYMIARY [mm]
	grubość linii początku rozjazdu kreska a odstęp b odstęp c	0.18 2 1 1
12	tekst	1.8

Rozjazd łukowy dwustronny ze zwrotnicą nieuzależnioną		
NAZWA WARSTWY	układ torowy	
ATRYBUTY GRAFICZNE	UWAGI	
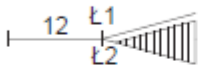		
ELEMENTY PRZEDSTAWIENIA GRAFICZNEGO		
ELEMENT	OPIS ELEMENTU	WYMIARY [mm]
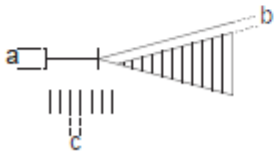	grubość linii początku rozjazdu kreska a odstęp b odstęp c	0.18 2 1 1
12	tekst	1.8

Rozjazd podwójny krzyżowy ze zwrotnicami uzależnionymi		
NAZWA WARSTWY	układ torowy	
ATRYBUTY GRAFICZNE	UWAGI	
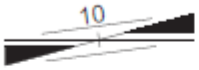 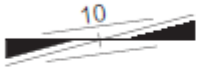	Zasadnicze położenie zwrotnic na tor główny. Zasadnicze położenie zwrotnic na tor odgałęźny.	
ELEMENTY PRZEDSTAWIENIA GRAFICZNEGO		
ELEMENT	OPIS ELEMENTU	WYMIARY [mm]
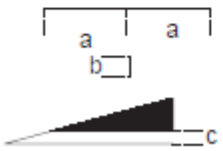	grubość linii oznaczenia kierucku zjazdu grubość linii punktu matematycznego rozjazdu długość odcinka a kreska b odstęp c	0.18 0.18 8 2 1
10	tekst	1.8

Rozjazd pojedynczy krzyżowy		
NAZWA WARSTWY	układ torowy	
ATRYBUTY GRAFICZNE	UWAGI	
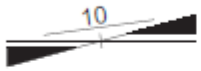		
ELEMENTY PRZEDSTAWIENIA GRAFICZNEGO		
ELEMENT	OPIS ELEMENTU	WYMIARY [mm]
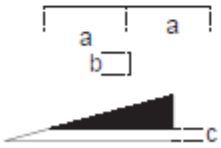	grubość linii oznaczenia kierucku zjazdu grubość linii punktu matematycznego rozjazdu długość odcinka a kreska b odstęp c	0.18 0.18 8 2 1
10	tekst	1.8

Rozjazd podwójny krzyżowy ze zwrotnicami nieuzależnionymi		
NAZWA WARSTWY	układ torowy	
ATRYBUTY GRAFICZNE	UWAGI	
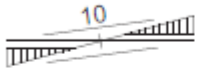		
ELEMENTY PRZEDSTAWIENIA GRAFICZNEGO		
ELEMENT	OPIS ELEMENTU	WYMIARY [mm]
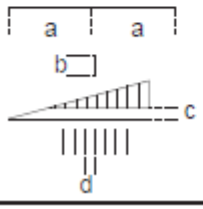	grubość linii oznaczenia kierunku zjazdu grubość linii punktu matematycznego rozjazdu długość odcinka a kreska b odstęp c odstęp d	0.18 0.18 8 2 1 1
10	tekst	1.8

Rozjazd podwójny krzyżowy z jedną parą zwrotnic uzależnioną		
NAZWA WARSTWY	układ torowy	
ATRYBUTY GRAFICZNE	UWAGI	
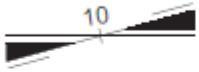		
ELEMENTY PRZEDSTAWIENIA GRAFICZNEGO		
ELEMENT	OPIS ELEMENTU	WYMIARY [mm]
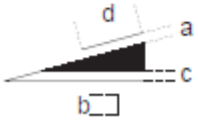	grubość linii oznaczenia kierunku zjazdu grubość linii punktu matematycznego rozjazdu odstęp a kreska b odstęp c długość d	0.18 0.18 1 2 1 6
10	tekst	1.8

Rozjazd podwójny krzyżowy nie oddany do użytku		
NAZWA WARSTWY	układ torowy	
ATRYBUTY GRAFICZNE	UWAGI	
		
ELEMENTY PRZEDSTAWIENIA GRAFICZNEGO		
ELEMENT	OPIS ELEMENTU	WYMIARY [mm]
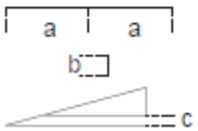	grubość linii oznaczenia kierunku zjazdu grubość linii punktu matematycznego rozjazdu długość odcinka a kreska b odstęp c	0.18 0.18 8 2 1
10	tekst	1.8

Skrzyżowanie torów kolejowych		
NAZWA WARSTWY	układ torowy	
ATRYBUTY GRAFICZNE	UWAGI	
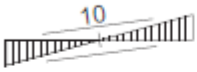		
ELEMENTY PRZEDSTAWIENIA GRAFICZNEGO		
ELEMENT	OPIS ELEMENTU	WYMIARY [mm]
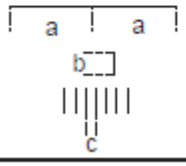	grubość linii oznaczenia kierunku zjazdu grubość linii punktu matematycznego rozjazdu długość odcinka a kreska b odstęp c	0.18 0.18 8 2 1
10	tekst	1.8

Ukres (wskaźnik W-17)		
NAZWA WARSTWY	układ torowy	
ATRYBUTY GRAFICZNE	UWAGI	
ELEMENTY PRZEDSTAWIENIA GRAFICZNEGO		
ELEMENT	OPIS ELEMENTU	WYMIARY [mm]
	grubość linii	1.8

Poduszka piaskowa		
NAZWA WARSTWY	układ torowy	
ATRYBUTY GRAFICZNE	UWAGI	
ELEMENTY PRZEDSTAWIENIA GRAFICZNEGO		
ELEMENT	OPIS ELEMENTU	WYMIARY [mm]
	grubość linii średnica punktów	0.18 0.18

Kozioł oporowy		
NAZWA WARSTWY	układ torowy	
ATRYBUTY GRAFICZNE	UWAGI	
ELEMENTY PRZEDSTAWIENIA GRAFICZNEGO		
ELEMENT	OPIS ELEMENTU	WYMIARY [mm]
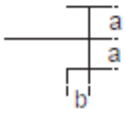	grubość linii długość odcinka a długość odcinka b	0.18 1.5 1

Międzytorze przystosowane do wsiadania i wysiadania podróżnych		
NAZWA WARSTWY	międzytorze	
ATRYBUTY GRAFICZNE	UWAGI	
ELEMENTY PRZEDSTAWIENIA GRAFICZNEGO		
ELEMENT	OPIS ELEMENTU	WYMIARY [mm]
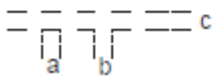	grubość linii kreska a odstęp b odstęp c	0.18 1 1 2

Semafor kształtowy		
NAZWA WARSTWY	sygnalizator	
ATRYBUTY GRAFICZNE	UWAGI	
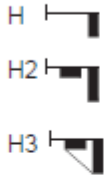	Jednoramienny Dwuramienny Dwuramienny sprzężony	
ELEMENTY PRZEDSTAWIENIA GRAFICZNEGO		
ELEMENT	OPIS ELEMENTU	WYMIARY [mm]
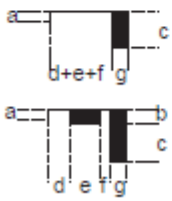	grubość linii długość a długość b długość c długość d długość e długość f długość g	0.18 2 1.5 3.5 2 3 1 1.5
H	tekst	

Semafor świetlny	
NAZWA WARSTWY	sygnalizator
ATRYBUTY GRAFICZNE	UWAGI
A C2 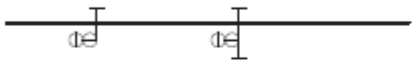	symbol szczegółowy zgodnie z Ie-4 (WTB E-10 (WTB E-10) załącznik 2

ELEMENTY PRZEDSTAWIENIA GRAFICZNEGO		
ELEMENT	OPIS ELEMENTU	WYMIARY [mm]
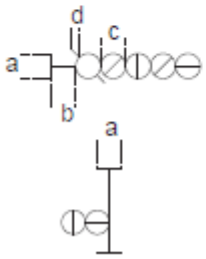	grubość linii długość a długość b średnica c długość d	0.18 2 2 2 1
C2	tekst	0.18

Tarcza ostrzegawcza świetlna	
NAZWA WARSTWY	sygnalizator
ATRYBUTY GRAFICZNE	UWAGI
ToB ToC	sygnał V_0, $V_{40/60}$ sygnał V_0, $V_{40/60}$, V_{max}

ELEMENTY PRZEDSTAWIENIA GRAFICZNEGO		
ELEMENT	OPIS ELEMENTU	WYMIARY [mm]
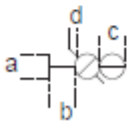	grubość linii długość a długość b średnica c długość d	0.18 2 2 2 1
ToB	tekst	1.8

Tarcza ostrzegawcza kształtowa		
NAZWA WARSTWY	sygnalizator	
ATRYBUTY GRAFICZNE	UWAGI	
ToA ToA ToC	dwustawna trzystawna nieruchoma	
ELEMENTY PRZEDSTAWIENIA GRAFICZNEGO		
ELEMENT	OPIS ELEMENTU	WYMIARY [mm]
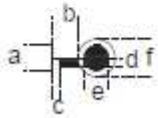	grubosc linii długość a długość b długość c długość d średnica e średnica f	0.18 2 3 3 1 2 3
ToA	tekst	1.8

Tarcza manewrowa kształtowa		
NAZWA WARSTWY	sygnalizator	
ATRYBUTY GRAFICZNE	UWAGI	
Tm1		
ELEMENTY PRZEDSTAWIENIA GRAFICZNEGO		
ELEMENT	OPIS ELEMENTU	WYMIARY [mm]
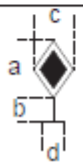	grubość linii wielkość a długość b wielkość c długość d	0.18 5 2 3.5 2
Tm1	tekst	1.8

Tarcza manewrowa świetlna		
NAZWA WARSTWY	sygnalizator	
ATRYBUTY GRAFICZNE	UWAGI	
Tm2 ⊢⊗ Tm3 ⊢⊗	- wysoki - karzełkowy	
ELEMENTY PRZEDSTAWIENIA GRAFICZNEGO		
ELEMENT	OPIS ELEMENTU	WYMIARY [mm]
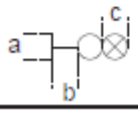	grubość linii długość a długość b średnica c	2 2 2 2
Tm2	tekst	1.8

Tarcza rozrządowa		
NAZWA WARSTWY	sygnalizator	
ATRYBUTY GRAFICZNE	UWAGI	
 	kształtowa świetlna	
ELEMENTY PRZEDSTAWIENIA GRAFICZNEGO		
ELEMENT	OPIS ELEMENTU	WYMIARY [mm]
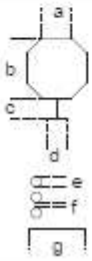	grubość linii długość a wielkość b długość c długość d średnica e odstęp f długość g grubość elementu g	0.18 3 6 2 2 1 0.5 8 0.35

Tarcza ostrzegawcza przejazdowa		
NAZWA WARSTWY	sygnalizator	
ATRYBUTY GRAFICZNE	UWAGI	
126 131N		
ELEMENTY PRZEDSTAWIENIA GRAFICZNEGO		
ELEMENT	OPIS ELEMENTU	WYMIARY [mm]
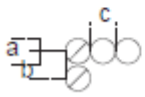	grubość linii długość a długość b średnica c	2 2 2 2
126	tekst	1.8

Tarcza zaporowa Z1		
NAZWA WARSTWY	sygnalizator	
ATRYBUTY GRAFICZNE	UWAGI	
ELEMENTY PRZEDSTAWIENIA GRAFICZNEGO		
ELEMENT	OPIS ELEMENTU	WYMIARY [mm]
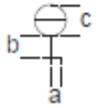	grubość linii długość a długość b średnica c	0.18 2 2 3

Wskaźnik granicy przetaczania W5		
NAZWA WARSTWY	wskaźniki	
ATRYBUTY GRAFICZNE	UWAGI	
ELEMENTY PRZEDSTAWIENIA GRAFICZNEGO		
ELEMENT	OPIS ELEMENTU	WYMIARY [mm]
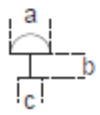	grubość linii wielkość a długość b długość c	0.18 3.5 2 2

Wskaźnik ustawienia tarczy ostrzegawczej W1		
NAZWA WARSTWY	wskaźniki	
ATRYBUTY GRAFICZNE	UWAGI	
ELEMENTY PRZEDSTAWIENIA GRAFICZNEGO		
ELEMENT	OPIS ELEMENTU	WYMIARY [mm]
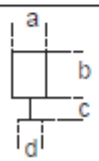	grubość linii obrysu symbolu długość a długość b długość c długość d grubość linii ukośnych wewnątrz znaku	0.18 3 4 2 2 0.35

Wskaźnik W11a		
NAZWA WARSTWY	wskaźniki	
ATRYBUTY GRAFICZNE	UWAGI	
ELEMENTY PRZEDSTAWIENIA GRAFICZNEGO		
ELEMENT	OPIS ELEMENTU	WYMIARY [mm]
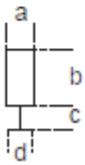	grubość linii symbolu długość a długość b długość c długość d grubość linii ukośnych wewnątrz symbolu odległość linii wewnątrz znaku	0.18 2.5 5 2 2 0.35 1

Wskaźnik W11b		
NAZWA WARSTWY	wskaźniki	
ATRYBUTY GRAFICZNE	UWAGI	
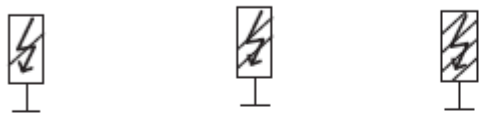		
ELEMENTY PRZEDSTAWIENIA GRAFICZNEGO		
ELEMENT	OPIS ELEMENTU	WYMIARY [mm]
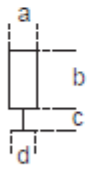	grubość linii symbolu długość a długość b długość c długość d grubość linii ukośnych wewnątrz symbolu odległość linii wewnątrz znaku	0.18 2.5 5 2 2 0.35 1
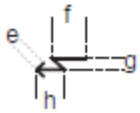	grubość linii symbolu długość e długość f szerokość g długość h	0.50 0.7 2.5 1 2

Wskaźnik W11p		
NAZWA WARSTWY	wskaźniki	
ATRYBUTY GRAFICZNE	UWAGI	
ELEMENTY PRZEDSTAWIENIA GRAFICZNEGO		
ELEMENT	OPIS ELEMENTU	WYMIARY [mm]
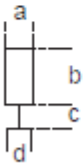	grubość linii symbolu długość a długość b długość c długość d	0.18 2.5 5 2 2
	grubość linii symbolu długość e odstęp pomiędzy symbolami	0.18 1.25 0.2

Wskaźnik W15		
NAZWA WARSTWY	wskaźniki	
ATRYBUTY GRAFICZNE	UWAGI	
ELEMENTY PRZEDSTAWIENIA GRAFICZNEGO		
ELEMENT	OPIS ELEMENTU	WYMIARY [mm]
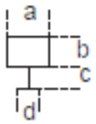	grubość linii symbolu długość a długość b długość c długość d	0.18 4 3 2 2

Wskaźnik W24 (wyjazd na tor przeciwny do zasadniczego)		
NAZWA WARSTWY	wskaźniki	
ATRYBUTY GRAFICZNE	UWAGI	
ELEMENTY PRZEDSTAWIENIA GRAFICZNEGO		
ELEMENT	OPIS ELEMENTU	WYMIARY [mm]
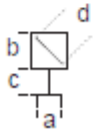	grubość linii symbolu długość a długość b długość c długość d grubość linii wewnątrz znaku	0.18 2 3 2 3 0.35

Wskaźnik zatrzymania się czoła pociągu W4		
NAZWA WARSTWY	wskaźniki	
ATRYBUTY GRAFICZNE	UWAGI	
ELEMENTY PRZEDSTAWIENIA GRAFICZNEGO		
ELEMENT	OPIS ELEMENTU	WYMIARY [mm]
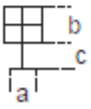	grubość linii symbolu długość a długość b długość c grubość linii krzyża wewnątrz znaku	0.18 2 3 2 0.35

Wskaźnik W2, W18, W19, W20, W21, W26, W27a		
NAZWA WARSTWY	wskaźniki	
ATRYBUTY GRAFICZNE	UWAGI	
	wewnątrz symbolu umieszcza się literę lub liczbę albo symbol odpowiedniego wskaźnika	
ELEMENTY PRZEDSTAWIENIA GRAFICZNEGO		
ELEMENT	OPIS ELEMENTU	WYMIARY [mm]
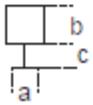	grubość linii symbolu długość a długość b długość c	0.18 2 3 2

Wskaźnik W3		
NAZWA WARSTWY	wskaźniki	
ATRYBUTY GRAFICZNE	UWAGI	
ELEMENTY PRZEDSTAWIENIA GRAFICZNEGO		
ELEMENT	OPIS ELEMENTU	WYMIARY [mm]
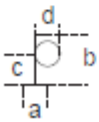	grubość linii symbolu długość a długość b długość c średnica d	0.18 2 6 3 2

Wskaźnik dawania sygnału baczność W6, W6a i W6b	
NAZWA WARSTWY	wskaźniki
ATRYBUTY GRAFICZNE	UWAGI
	wewnątrz symbolu należy umieścić odpowiedni symbol dla danego wskaźnika

ELEMENTY PRZEDSTAWIENIA GRAFICZNEGO		
ELEMENT	OPIS ELEMENTU	WYMIARY [mm]
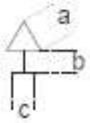	grubość linii symbolu bok trójkąta a długość b długość c	0.18 3 2 2

Wskaźnik W-32 zatrzymania czoła pociągu o długości określonej tym wskaźnikiem	
NAZWA WARSTWY	wskaźniki
ATRYBUTY GRAFICZNE	UWAGI

ELEMENTY PRZEDSTAWIENIA GRAFICZNEGO		
ELEMENT	OPIS ELEMENTU	WYMIARY [mm]
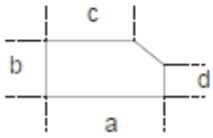	grubość linii długość a długość b długość c długość d	0.18 8 4 6 2
200	tekst	1.8

Nastawnia ręczna parterowa	
NAZWA WARSTWY	budynek
ATRYBUTY GRAFICZNE	UWAGI
	podłoga do wys. 2.0 m nad główką szyny

ELEMENTY PRZEDSTAWIENIA GRAFICZNEGO		
ELEMENT	OPIS ELEMENTU	WYMIARY [mm]
	grubość linii odstęp a odstęp b średnica c grubość d	0.5 2 1 1 1

Nastawnia parterowa mechaniczna		
NAZWA WARSTWY	budynek	
ATRYBUTY GRAFICZNE	UWAGI	
	podłoga do wys. 2.0 m nad główką szyny	
ELEMENTY PRZEDSTAWIENIA GRAFICZNEGO		
ELEMENT	OPIS ELEMENTU	WYMIARY [mm]
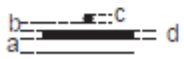	grubość linii odstęp a odstęp b średnica c grubość d odstęp linii skośnych	0.5 2 1 1 1 1

Nastawnia parterowa elektryczna		
NAZWA WARSTWY	budynek	
ATRYBUTY GRAFICZNE	UWAGI	
	podłoga do wys. 2.0 m nad główką szyny	
ELEMENTY PRZEDSTAWIENIA GRAFICZNEGO		
ELEMENT	OPIS ELEMENTU	WYMIARY [mm]
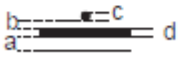	grubość linii odstęp a odstęp b średnica c grubość d odstęp linii skośnych	0.5 2 1 1 1 1

Nastawnia piętrowa ręczna		
NAZWA WARSTWY	budynek	
ATRYBUTY GRAFICZNE	UWAGI	
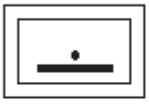	podłoga wyżej niż 2.0 m nad główką szyny	
ELEMENTY PRZEDSTAWIENIA GRAFICZNEGO		
ELEMENT	OPIS ELEMENTU	WYMIARY [mm]
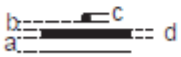	grubość linii odstęp linii równoległych odstęp a odstęp b średnica c grubość d	0.5 1 2 1 1 1

Nastawnia piętrowa mechaniczna		
NAZWA WARSTWY	budynek	
ATRYBUTY GRAFICZNE	UWAGI	
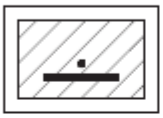	podłoga wyżej niż 2.0 m nad główką szyny	
ELEMENTY PRZEDSTAWIENIA GRAFICZNEGO		
ELEMENT	OPIS ELEMENTU	WYMIARY [mm]
	grubość linii odstęp linii równoległych odstęp a odstęp b średnica c grubość d odstęp linii skośnych	0.5 1 2 1 1 1 1

Nastawnia piętrowa elektryczna		
NAZWA WARSTWY	budynek	
ATRYBUTY GRAFICZNE	UWAGI	
	podłoga wyżej niż 2.0 m nad główką szyny	
ELEMENTY PRZEDSTAWIENIA GRAFICZNEGO		
ELEMENT	OPIS ELEMENTU	WYMIARY [mm]
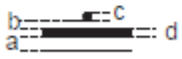	grubość linii odstęp linii równoległych odstęp a odstęp b średnica c grubość d odstęp linii skośnych	0.5 1 2 1 1 1 1

Nastawnia parterowa komputerowa		
NAZWA WARSTWY	budynek	
ATRYBUTY GRAFICZNE	UWAGI	
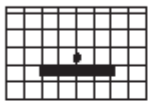	podłoga do wys. 2.0 m nad główką szyny	
ELEMENTY PRZEDSTAWIENIA GRAFICZNEGO		
ELEMENT	OPIS ELEMENTU	WYMIARY [mm]
	grubość linii odstęp a odstęp b średnica c grubość d odstęp linii prostopoadłych	0.5 2 1 1 1 1

Nastawnia piętrowa komputerowa		
NAZWA WARSTWY	budynek	
ATRYBUTY GRAFICZNE	UWAGI	
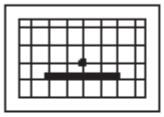	podłoga wyżej niż 2.0 m nad główką szyny	
ELEMENTY PRZEDSTAWIENIA GRAFICZNEGO		
ELEMENT	OPIS ELEMENTU	WYMIARY [mm]
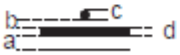	grubość linii odstęp linii równoległych odstęp a odstęp b średnica c grubość d odstęp linii prostopadłych	0.5 1 2 1 1 1 1

Budynek		
NAZWA WARSTWY	budynek	
ATRYBUTY GRAFICZNE	UWAGI	
ELEMENTY PRZEDSTAWIENIA GRAFICZNEGO		
ELEMENT	OPIS ELEMENTU	WYMIARY [mm]
	grubość linii	0.18

Hale dworcowe nad torami kolejowymi		
NAZWA WARSTWY	budynek	
ATRYBUTY GRAFICZNE	UWAGI	
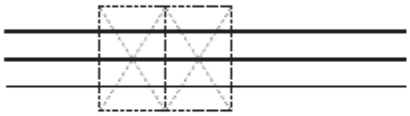		
ELEMENTY PRZEDSTAWIENIA GRAFICZNEGO		
ELEMENT	OPIS ELEMENTU	WYMIARY [mm]
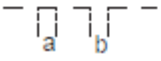	grubość linii kreska a odstęp b	0.18 1 1

Wiata		
NAZWA WARSTWY	budowla	
ATRYBUTY GRAFICZNE	UWAGI	
ELEMENTY PRZEDSTAWIENIA GRAFICZNEGO		
ELEMENT	OPIS ELEMENTU	WYMIARY [mm]
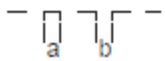	grubość linii kreska a odstęp b	0.18 1 1

Przejście dla pieszych lub przejazd w poziomie torów kolejowych		
NAZWA WARSTWY	budowla	
ATRYBUTY GRAFICZNE	UWAGI	
ELEMENTY PRZEDSTAWIENIA GRAFICZNEGO		
ELEMENT	OPIS ELEMENTU	WYMIARY [mm]
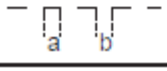	grubość linii kreska a odstęp b	0.18 2 1

Schody ze spocznikami		
NAZWA WARSTWY	budowla	
ATRYBUTY GRAFICZNE	UWAGI	
ELEMENTY PRZEDSTAWIENIA GRAFICZNEGO		
ELEMENT	OPIS ELEMENTU	WYMIARY [mm]
	grubość linii	0.18

Most		
NAZWA WARSTWY	budowla	
ATRYBUTY GRAFICZNE	UWAGI	
ELEMENTY PRZEDSTAWIENIA GRAFICZNEGO		
ELEMENT	OPIS ELEMENTU	WYMIARY [mm]
	grubość linii	0.18

Przejście piesze pod torami kolejowymi		
NAZWA WARSTWY	budowla	
ATRYBUTY GRAFICZNE	UWAGI	
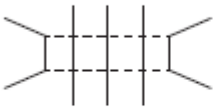		
ELEMENTY PRZEDSTAWIENIA GRAFICZNEGO		
ELEMENT	OPIS ELEMENTU	WYMIARY [mm]
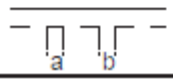	grubość linii kreska a odstęp b	0.18 1 1

Przejście piesze nad torami kolejowymi		
NAZWA WARSTWY	budowla	
ATRYBUTY GRAFICZNE	UWAGI	
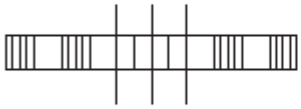		
ELEMENTY PRZEDSTAWIENIA GRAFICZNEGO		
ELEMENT	OPIS ELEMENTU	WYMIARY [mm]
	grubość linii	0.18

Linia kolejowa w tunelu		
NAZWA WARSTWY	budowla	
ATRYBUTY GRAFICZNE	UWAGI	
		
ELEMENTY PRZEDSTAWIENIA GRAFICZNEGO		
ELEMENT	OPIS ELEMENTU	WYMIARY [mm]
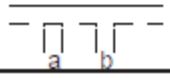	grubość linii kreska a odstęp b	0.18 1 1

Tunel pod linia kolejową		
NAZWA WARSTWY	budowla	
ATRYBUTY GRAFICZNE	UWAGI	
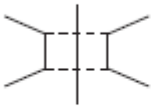		
ELEMENTY PRZEDSTAWIENIA GRAFICZNEGO		
ELEMENT	OPIS ELEMENTU	WYMIARY [mm]
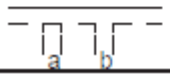	grubość linii kreska a odstęp b	0.18 1 1

Przepust		
NAZWA WARSTWY	budowla	
ATRYBUTY GRAFICZNE	UWAGI	
ELEMENTY PRZEDSTAWIENIA GRAFICZNEGO		
ELEMENT	OPIS ELEMENTU	WYMIARY [mm]
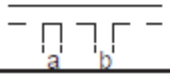	grubość linii kreska a odstęp b	0.18 1 1

Skrzyżowanie linii kolejowej z drogą w dwóch poziomach		
NAZWA WARSTWY	budowla	
ATRYBUTY GRAFICZNE	UWAGI	
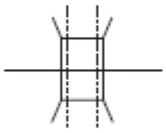	Linia kolejowa w poziomie górnym	
ELEMENTY PRZEDSTAWIENIA GRAFICZNEGO		
ELEMENT	OPIS ELEMENTU	WYMIARY [mm]
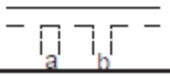	grubość linii kreska a odstęp b	0.18 1 1

Skrzyżowanie linii kolejowej z drogą w dwóch poziomach		
NAZWA WARSTWY	budowla	
ATRYBUTY GRAFICZNE	UWAGI	
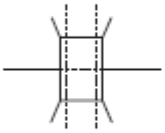	Linia kolejowa w poziomie dolnym	
ELEMENTY PRZEDSTAWIENIA GRAFICZNEGO		
ELEMENT	OPIS ELEMENTU	WYMIARY [mm]
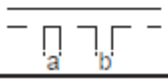	grubość linii kreska a odstęp b	0.18 1 1

Skrzyżowanie dwóch torów kolejowych w różnych poziomach		
NAZWA WARSTWY	budowla	
ATRYBUTY GRAFICZNE	UWAGI	
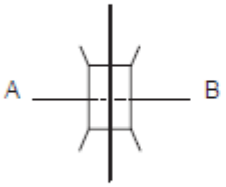	A-B w poziomie dolnym	
ELEMENTY PRZEDSTAWIENIA GRAFICZNEGO		
ELEMENT	OPIS ELEMENTU	WYMIARY [mm]
	grubość linii	0.18

Wieża wodna		
NAZWA WARSTWY	budowla	
ATRYBUTY GRAFICZNE	UWAGI	
ELEMENTY PRZEDSTAWIENIA GRAFICZNEGO		
ELEMENT	OPIS ELEMENTU	WYMIARY [mm]
	grubość linii	0.18
w	tekst	1.8

Kontener		
NAZWA WARSTWY	budowla	
ATRYBUTY GRAFICZNE	UWAGI	
ELEMENTY PRZEDSTAWIENIA GRAFICZNEGO		
ELEMENT	OPIS ELEMENTU	WYMIARY [mm]
	grubość linii	0.18
r	tekst	1.8

Wieża GSM-R		
NAZWA WARSTWY	budowle	
ATRYBUTY GRAFICZNE	UWAGI	
	kratownica betonowa lub stalowa	
ELEMENTY PRZEDSTAWIENIA GRAFICZNEGO		
ELEMENT	OPIS ELEMENTU	WYMIARY [mm]
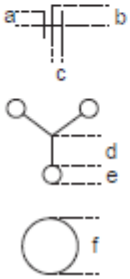	grubość linii długość a długość b długość c długość d średnica e średnica f	0.18 2 4 2.5 3.5 1.5 10

Stacja przepompowni gazu		
NAZWA WARSTWY	budowla	
ATRYBUTY GRAFICZNE	UWAGI	
ELEMENTY PRZEDSTAWIENIA GRAFICZNEGO		
ELEMENT	OPIS ELEMENTU	WYMIARY [mm]
	grubość linii średnica a średnica b	0.18 5 7
st.p.g.	tekst	1.8

Odłącznik jednobiegunowy		
NAZWA WARSTWY	energetyka trakcyjna	
ATRYBUTY GRAFICZNE	UWAGI	
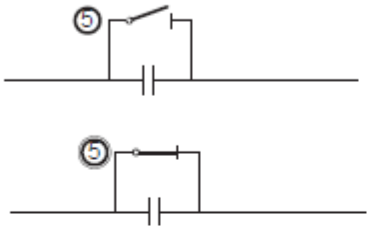	Odłącznik otwarty o napędzie ręcznym Odłącznik zamknięty o napędzie silnikowym sterowanym lokalnie lub zdalnie	
ELEMENTY PRZEDSTAWIENIA GRAFICZNEGO		
ELEMENT	OPIS ELEMENTU	WYMIARY [mm]
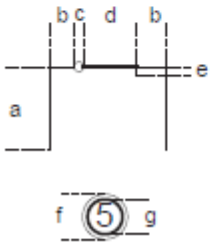	grubość linii długość a długość b średnica c długość d długość e średnica f średnica g	0.18 10 3 1.5 5 1 3 5
5	tekst	1.8

Izolator sekcyjny		
NAZWA WARSTWY	energetyka trakcyjna	
ATRYBUTY GRAFICZNE	UWAGI	
		
ELEMENTY PRZEDSTAWIENIA GRAFICZNEGO		
ELEMENT	OPIS ELEMENTU	WYMIARY [mm]
	odstęp a długość b	2 3

Oś toru zelektryfikowanego (z siecią trakcyjną)		
NAZWA WARSTWY	energetyka trakcyjna	
ATRYBUTY GRAFICZNE	UWAGI	
ELEMENTY PRZEDSTAWIENIA GRAFICZNEGO		
ELEMENT	OPIS ELEMENTU	WYMIARY [mm]
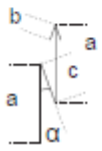	odstęp a odstęp b odstęp c kąt α 20 st.	15 3 8

Latarnia		
NAZWA WARSTWY	energetyka nietrakcyjna	
ATRYBUTY GRAFICZNE	UWAGI	
ELEMENTY PRZEDSTAWIENIA GRAFICZNEGO		
ELEMENT	OPIS ELEMENTU	WYMIARY [mm]
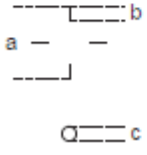	grubość linii długość a długość b średnica c	0.18 5 1 1

Dźwig obrotowy		
NAZWA WARSTWY	dźwig	
ATRYBUTY GRAFICZNE	UWAGI	
ELEMENTY PRZEDSTAWIENIA GRAFICZNEGO		
ELEMENT	OPIS ELEMENTU	WYMIARY [mm]
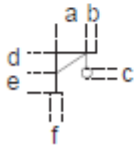	długość a długość b średnica c długość d długość e długość f	4 2 1.5 3 3 2

Dźwig bramowy		
NAZWA WARSTWY	dźwig	
ATRYBUTY GRAFICZNE	UWAGI	
ELEMENTY PRZEDSTAWIENIA GRAFICZNEGO		
ELEMENT	OPIS ELEMENTU	WYMIARY [mm]
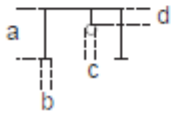	długość a długość b średnica c długość d	6 2 1.5 1.5

Dźwig wieżowy		
NAZWA WARSTWY	dźwig	
ATRYBUTY GRAFICZNE	UWAGI	
ELEMENTY PRZEDSTAWIENIA GRAFICZNEGO		
ELEMENT	OPIS ELEMENTU	WYMIARY [mm]
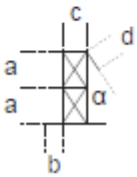	długość a długość b długość c długość d kąt α 25 st.	3 2 2.5 2

Kanał oczystkowy z elektrowciągiem		
NAZWA WARSTWY	kanał oczystkowy	
ATRYBUTY GRAFICZNE	UWAGI	
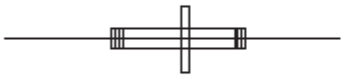		
ELEMENTY PRZEDSTAWIENIA GRAFICZNEGO		
ELEMENT	OPIS ELEMENTU	WYMIARY [mm]
	grubość linii	0.18

Kanał oczystkowy skibowy		
NAZWA WARSTWY	kanał oczystkowy	
ATRYBUTY GRAFICZNE	UWAGI	
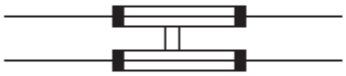		
ELEMENTY PRZEDSTAWIENIA GRAFICZNEGO		
ELEMENT	OPIS ELEMENTU	WYMIARY [mm]
	grubość linii	0.18

Kanał oczystkowy z dołem żużlowym		
NAZWA WARSTWY	kanał oczystkowy	
ATRYBUTY GRAFICZNE	UWAGI	
ELEMENTY PRZEDSTAWIENIA GRAFICZNEGO		
ELEMENT	OPIS ELEMENTU	WYMIARY [mm]
	grubość linii	0.18

Strefa oddziaływania bezzłączowych obwodów torowych SOT		
NAZWA WARSTWY	urządzenia oddziaływania	
ATRYBUTY GRAFICZNE	UWAGI	
ELEMENTY PRZEDSTAWIENIA GRAFICZNEGO		
ELEMENT	OPIS ELEMENTU	WYMIARY [mm]
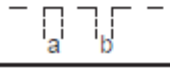	grubość linii kreska a odstęp b	0.18 1 1

Złącze izolowane		
NAZWA WARSTWY	Złącze izolowane	
ATRYBUTY GRAFICZNE	UWAGI	
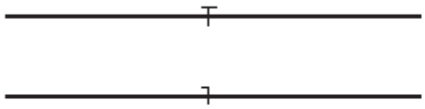	- na styku dwóch szyn izolowanych - na styku szynu izolowanej z nieizolowaną (szyna izolowana po lewej)	
ELEMENTY PRZEDSTAWIENIA GRAFICZNEGO		
ELEMENT	OPIS ELEMENTU	WYMIARY [mm]
	długość a długość b	0.75 3

Elektroniczny obwód nakładany		
NAZWA WARSTWY	Elektryczny obwód nakładany	
ATRYBUTY GRAFICZNE	UWAGI	
ELEMENTY PRZEDSTAWIENIA GRAFICZNEGO		
ELEMENT	OPIS ELEMENTU	WYMIARY [mm]
	grubość linii długość a bok trójkąta b	0.18 3 2.5

Licznik osi		
NAZWA WARSTWY	licznik osi	
ATRYBUTY GRAFICZNE	UWAGI	
ELEMENTY PRZEDSTAWIENIA GRAFICZNEGO		
ELEMENT	OPIS ELEMENTU	WYMIARY [mm]
	grubość linii kreska a odstęp b średnica c	0.18 4 2 1

Czujnik magnetyczny		
NAZWA WARSTWY	Czujnik magnetyczny	
ATRYBUTY GRAFICZNE	UWAGI	
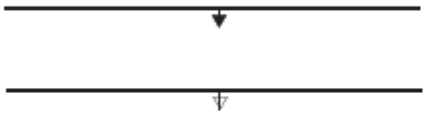	pojedyńczy podwójny	
ELEMENTY PRZEDSTAWIENIA GRAFICZNEGO		
ELEMENT	OPIS ELEMENTU	WYMIARY [mm]
	grubość linii bok trójkąta a	0.18 2.5

Elektromagnes torowy SHP		
NAZWA WARSTWY	SHP	
ATRYBUTY GRAFICZNE	UWAGI	
ELEMENTY PRZEDSTAWIENIA GRAFICZNEGO		
ELEMENT	OPIS ELEMENTU	WYMIARY [mm]
	wielkość a szerokość b	1 3

Peron		
NAZWA WARSTWY	peron	
ATRYBUTY GRAFICZNE	UWAGI	
	jednokrawędziowy dwukrawędziowy	
ELEMENTY PRZEDSTAWIENIA GRAFICZNEGO		
ELEMENT	OPIS ELEMENTU	WYMIARY [mm]
	grubość linii odstęp a	0.18 0.7
per. 1	tekst	1.8

Wykolejnica		
NAZWA WARSTWY	wykolejnica	
ATRYBUTY GRAFICZNE	UWAGI	
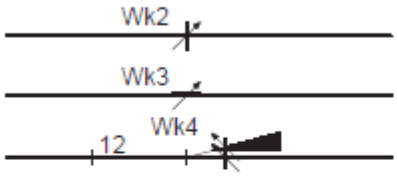		
ELEMENTY PRZEDSTAWIENIA GRAFICZNEGO		
ELEMENT	OPIS ELEMENTU	WYMIARY [mm]
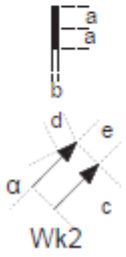	wielkość a szerokość b długość odcinka c wysokość grota d szerokość e wartość kąta α 20 st.	2 0.5 6 2 1.5

Rogatki z napędem mechanicznym		
NAZWA WARSTWY	napęd rogatkowy	
ATRYBUTY GRAFICZNE	UWAGI	
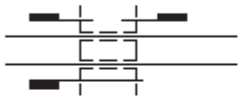		
ELEMENTY PRZEDSTAWIENIA GRAFICZNEGO		
ELEMENT	OPIS ELEMENTU	WYMIARY [mm]
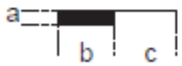	grubość linii wymiar a długość b wymiar c wysunięty poza drogę	0.18 1 4

Rogatki z napędem elektrycznym		
NAZWA WARSTWY	napęd rogatkowy	
ATRYBUTY GRAFICZNE	UWAGI	
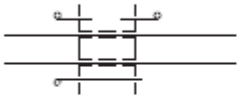		
ELEMENTY PRZEDSTAWIENIA GRAFICZNEGO		
ELEMENT	OPIS ELEMENTU	WYMIARY [mm]
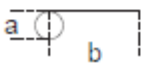	grubość linii wymiar a wymiar b wysunięty poza drogę	0.18 1 4

Obrotnica		
NAZWA WARSTWY	obrotnica	
ATRYBUTY GRAFICZNE	UWAGI	
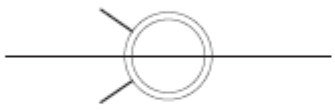		
ELEMENTY PRZEDSTAWIENIA GRAFICZNEGO		
ELEMENT	OPIS ELEMENTU	WYMIARY [mm]
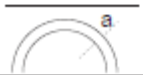	grubość linii odległość a	0.18 1

Przesuwnica	
NAZWA WARSTWY	przesuwnica
ATRYBUTY GRAFICZNE	UWAGI
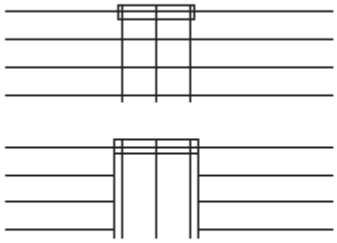	w poziomie szyn wgłębna

ELEMENTY PRZEDSTAWIENIA GRAFICZNEGO		
ELEMENT	OPIS ELEMENTU	WYMIARY [mm]
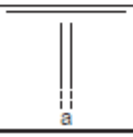	grubość linii odległość a	0.18 1

Żuraw wodny	
NAZWA WARSTWY	żuraw wodny
ATRYBUTY GRAFICZNE	UWAGI
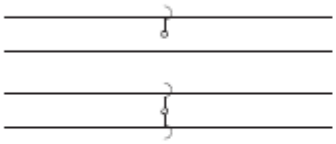	do obsługi jednego toru do obsługi dwóch torów

ELEMENTY PRZEDSTAWIENIA GRAFICZNEGO		
ELEMENT	OPIS ELEMENTU	WYMIARY [mm]
	grubość linii średnica a długość b odległość c	0.18 1 3 3

Hydrant pożarowy	
NAZWA WARSTWY	hydrant
ATRYBUTY GRAFICZNE	UWAGI

ELEMENTY PRZEDSTAWIENIA GRAFICZNEGO		
ELEMENT	OPIS ELEMENTU	WYMIARY [mm]
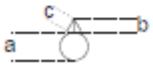	średnica a odległość b odległość c	3 1.5 1.5

Myjnia wagonów		
NAZWA WARSTWY	myjnia wagonów	
ATRYBUTY GRAFICZNE	UWAGI	
		
ELEMENTY PRZEDSTAWIENIA GRAFICZNEGO		
ELEMENT	OPIS ELEMENTU	WYMIARY [mm]
	grubość linii	0.18
myjnia	tekst	1.8

Waga		
NAZWA WARSTWY	waga	
ATRYBUTY GRAFICZNE	UWAGI	
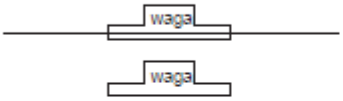	wagonowa wozowa	
ELEMENTY PRZEDSTAWIENIA GRAFICZNEGO		
ELEMENT	OPIS ELEMENTU	WYMIARY [mm]
	grubość linii	0.18
waga	tekst	1.8

Rampa		
NAZWA WARSTWY	rampa	
ATRYBUTY GRAFICZNE	UWAGI	
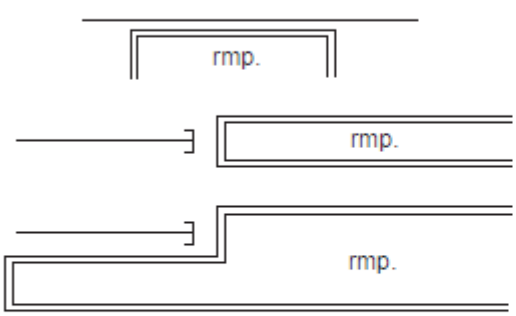	boczna czołowa boczno - czołowa b- beton, c- cegła, d- drewno, k- kamień, T- transporotwa	
ELEMENTY PRZEDSTAWIENIA GRAFICZNEGO		
ELEMENT	OPIS ELEMENTU	WYMIARY [mm]
a	grubość linii odstęp a	0.18 1
rmp.	tekst	1.8

Skrajnik	
NAZWA WARSTWY	skrajnik
ATRYBUTY GRAFICZNE	UWAGI
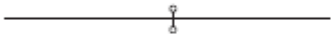	

ELEMENTY PRZEDSTAWIENIA GRAFICZNEGO		
ELEMENT	OPIS ELEMENTU	WYMIARY [mm]
	grubość linii średnica a	0.18 1

Wskaźnik kilometrowy i hektometrowy linii kolejowej	
NAZWA WARSTWY	kilometraż
ATRYBUTY GRAFICZNE	UWAGI
	Stabilizowany dla linii: jednotorowej dwutorowej z podaniem szerokości międzytorza Niestabilizowany dla linii: jednotorowej dwutorowej z podaniem szerokości międzytorza

ELEMENTY PRZEDSTAWIENIA GRAFICZNEGO		
ELEMENT	OPIS ELEMENTU	WYMIARY [mm]
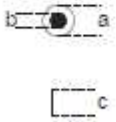	grubość linii średnica a średnica b długość c	0.18 3 1.5 3
12	tekst	2.5
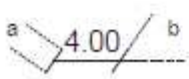	grubość linii długość a kąt b	0.18 2 55°
4.00	tekst	1.5

Wyrzutnia płozów hamulcowych		
NAZWA WARSTWY	wyrzutnia płozów hamulcowych	
ATRYBUTY GRAFICZNE	UWAGI	
ELEMENTY PRZEDSTAWIENIA GRAFICZNEGO		
ELEMENT	OPIS ELEMENTU	WYMIARY [mm]
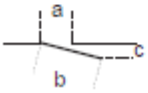	odstęp a długość b odstęp c	3 6 1.5

Drogi dojazdowe i place		
NAZWA WARSTWY	drogi	
ATRYBUTY GRAFICZNE	UWAGI	
ELEMENTY PRZEDSTAWIENIA GRAFICZNEGO		
ELEMENT	OPIS ELEMENTU	WYMIARY [mm]
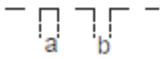	grubość linii kreska a odstęp b	0.18 2 1

Oś stacji		
NAZWA WARSTWY	opis	
ATRYBUTY GRAFICZNE	UWAGI	
Oś stacji km		
ELEMENTY PRZEDSTAWIENIA GRAFICZNEGO		
ELEMENT	OPIS ELEMENTU	WYMIARY [mm]
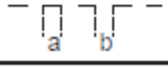	grubość linii kreska a odstęp b	0.40 2 2
8	tekst	2.5

Pochylenie niwelety	
NAZWA WARSTWY	opis
ATRYBUTY GRAFICZNE	UWAGI
	- w przypadku różnych pochyleń na sąsiednich torach.

ELEMENTY PRZEDSTAWIENIA GRAFICZNEGO		
ELEMENT	OPIS ELEMENTU	WYMIARY [mm]
	grubość linii średnica punktu długość odcinka a odstęp b	0.18 1 2 1
km 2.357 2.4 350	tekst tekst tekst	1.8 1.8 1.8

Hamulce torowe	
NAZWA WARSTWY	przytorowe urządzenia srk
ATRYBUTY GRAFICZNE	UWAGI
	zabudowane przy dwóch tokach szynowych zabudowane przy jednym toku szynowym

ELEMENTY PRZEDSTAWIENIA GRAFICZNEGO		
ELEMENT	OPIS ELEMENTU	WYMIARY [mm]
	grubość linii odległość od toru a	0.18 1

Balisa	
NAZWA WARSTWY	przytorowe urządzenia srk
ATRYBUTY GRAFICZNE	UWAGI
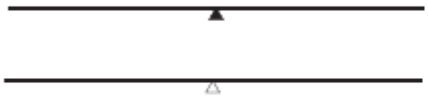	nieprzełączalna przełączalna

ELEMENTY PRZEDSTAWIENIA GRAFICZNEGO		
ELEMENT	OPIS ELEMENTU	WYMIARY [mm]
	grubość linii długość a	0.18 2.5

Granica okręgu nastawczego		
NAZWA WARSTWY	okręgi nastawcze	
ATRYBUTY GRAFICZNE	UWAGI	
ELEMENTY PRZEDSTAWIENIA GRAFICZNEGO		
ELEMENT	OPIS ELEMENTU	WYMIARY [mm]
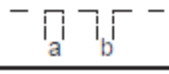	grubość linii kreska a odstęp b	0.35 2 2

Urządzenia do prób hamulcowych i podgrzewania składów		
NAZWA WARSTWY	uzbrojenie techniczne stacji	
ATRYBUTY GRAFICZNE	UWAGI	
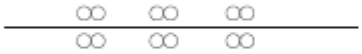		
ELEMENTY PRZEDSTAWIENIA GRAFICZNEGO		
ELEMENT	OPIS ELEMENTU	WYMIARY [mm]
	grubość linii średnica a	0.18 1.5

Dodatkowe urządzenia do sygnalizacji samoczynnej na przejeździe kolejowym		
NAZWA WARSTWY	sygnalizator drogowy	
ATRYBUTY GRAFICZNE	UWAGI	
 	dzwon buczek	
ELEMENTY PRZEDSTAWIENIA GRAFICZNEGO		
ELEMENT	OPIS ELEMENTU	WYMIARY [mm]
	grubość linii długość a	0.18 2

Krzyż św. Andrzeja		
NAZWA WARSTWY	sygnalizator drogowy	
ATRYBUTY GRAFICZNE	UWAGI	
	Na przejeździe kolejowym linii kolejowej: jednotorowej dwutorowej	
ELEMENTY PRZEDSTAWIENIA GRAFICZNEGO		
ELEMENT	OPIS ELEMENTU	WYMIARY [mm]
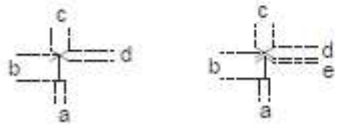	grubość linii długość a wysokość b szerokość c szerokość d odstęp e	0.18 1 2 3 1 0.5

Sygnalizacja samoczynna na przejeździe kolejowym		
NAZWA WARSTWY	sygnalizator drogowy	
ATRYBUTY GRAFICZNE	UWAGI	
	W zależności od kategorii przejazdu symbol sygnalizatora drogowego uzupełnić o oznaczenie krzyża św. Andrzeja	
ELEMENTY PRZEDSTAWIENIA GRAFICZNEGO		
ELEMENT	OPIS ELEMENTU	WYMIARY [mm]
	grubość linii długość a wysokość b szerokość c średnica d wymiar e Wymiary krzyża św. Andrzeja zgodne z opisem symbolu. Odstęp pomiędzy symbolami 1 mm.	0.18 2 3 5 1 0.5

Przebiegi pociągowe	
NAZWA WARSTWY	przebiegi pociągowe
ATRYBUTY GRAFICZNE	UWAGI
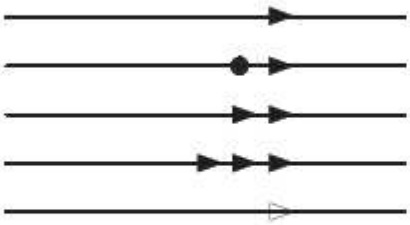	- wszystkich rodzajów w danym kierunku na terenie stacji i w kierunku zasadniczym na szlaku - wyłącznie podmiejskich - wyłącznie towarowych - w celach związanych z obsługą pociągów (komunikacyjne) - wszystkich pociągów w kierunku przeciwnym do zasadniczego

ELEMENTY PRZEDSTAWIENIA GRAFICZNEGO		
ELEMENT	OPIS ELEMENTU	WYMIARY [mm]
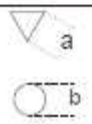	grubość linii bok trójkąta a średnica b	0.18 2.5 3

Telewizja użytkowa	
NAZWA WARSTWY	TV
ATRYBUTY GRAFICZNE	UWAGI

ELEMENTY PRZEDSTAWIENIA GRAFICZNEGO		
ELEMENT	OPIS ELEMENTU	WYMIARY [mm]
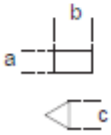	grubość linii długość a długość b długość c	0.18 2 3.5 2

Ogrodzenie	
NAZWA WARSTWY	budowla
ATRYBUTY GRAFICZNE	UWAGI

ELEMENTY PRZEDSTAWIENIA GRAFICZNEGO		
ELEMENT	OPIS ELEMENTU	WYMIARY [mm]
	grubość linii śtrdnica kropki rozstaw kropek	0.35 0.7 15

Elektryczne ogrzewanie rozjazdów		
NAZWA WARSTWY	EOR	
ATRYBUTY GRAFICZNE	UWAGI	
ELEMENTY PRZEDSTAWIENIA GRAFICZNEGO		
ELEMENT	OPIS ELEMENTU	WYMIARY [mm]
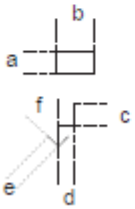	grubość linii długość a długość b długość c długość d długość e kąt f	0.18 2 3.5 2 1.5 1 45°
eor	tekst	1.8

Górka rozrządowa		
NAZWA WARSTWY	budowla	
ATRYBUTY GRAFICZNE	UWAGI	
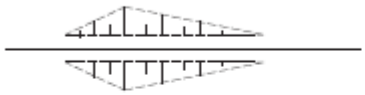		
ELEMENTY PRZEDSTAWIENIA GRAFICZNEGO		
ELEMENT	OPIS ELEMENTU	WYMIARY [mm]
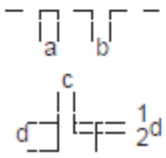	grubość linii długość a długość b odstęp c	0.18 2.5 1 5

Ściana oporowa		
NAZWA WARSTWY	budowla	
ATRYBUTY GRAFICZNE	UWAGI	
ELEMENTY PRZEDSTAWIENIA GRAFICZNEGO		
ELEMENT	OPIS ELEMENTU	WYMIARY [mm]
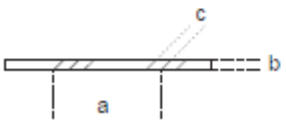	grubość linii długość a długość b średnica c	0.18 10 1 1

Mur oporowy		
NAZWA WARSTWY	budowla	
ATRYBUTY GRAFICZNE	UWAGI	
ELEMENTY PRZEDSTAWIENIA GRAFICZNEGO		
ELEMENT	OPIS ELEMENTU	WYMIARY [mm]
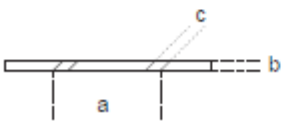	grubość linii długość a długość b średnica c	0.18 10 1 1

Kilometraż		
NAZWA WARSTWY	opis	
ATRYBUTY GRAFICZNE	UWAGI	
25.452 wiadukt drogowy 25.452	- w przypadku wiaduktu, mostu, przepustu, kładki, przejazdu (z pod. kategorii) oraz przejścia.	
ELEMENTY PRZEDSTAWIENIA GRAFICZNEGO		
ELEMENT	OPIS ELEMENTU	WYMIARY [mm]
a b	grubość linii kreska a odstęp b	0.18 2 2
25.452	tekst	2.5